PERFIL DA AGRICULTURA FAMILIAR NA PARAÍBA

OBSERVATÓRIO DA AGRICULTURA FAMILIAR DA PARAÍBA
(OAF-PB)

OUTUBRO DE 2022

DIEESE
DEPARTAMENTO INTERSINDICAL DE
ESTATÍSTICA E ESTUDOS SOCIOECONÔMICOS

SUMÁRIO

APRESENTAÇÃO 5

PERFIL GEOGRÁFICO, DEMOGRÁFICO E SOCIOECONÔMICO DA PARAÍBA 6

AGRICULTURA FAMILIAR NO NORDESTE E NA PARAÍBA 11

DADOS GERAIS 11

VALOR E COMPOSIÇÃO DA PRODUÇÃO AGRICULTURA FAMILIAR PARAIBANA, EM 2017 16

RADIOGRAFIA DA PRODUÇÃO DE ORIGEM ANIMAL NOS ESTABELECIMENTOS DA AGRICULTURA FAMILIAR NA PARAÍBA, EM 2017 19

Dedicação dos estabelecimentos 19

Valor da produção de origem animal, por tipo 20

RADIOGRAFIA DA PRODUÇÃO DE ORIGEM VEGETAL NOS ESTABELECIMENTOS DA AGRICULTURA FAMILIAR NA PARAÍBA, EM 2017 21

Lavouras temporária 22

Lavouras permanentes 22

Horticultura 22

Floricultura 23

Silvicultura 23

Extração vegetal 23

PRODUTOS COMERCIALIZADOS PELA AGROINDÚSTRIA FAMILIAR NA PARAÍBA, EM 2017 25

VALOR DAS DESPESAS DOS ESTABELECIMENTOS DA AGRICULTURA FAMILIAR PARAIBANA, EM 2017 26

UTILIZAÇÃO DE AGROTÓXICOS PELOS ESTABELECIMENTOS DA AGROPECUÁRIA PARAIBANA, EM 2017 28

OBTENÇÃO DE ORIENTAÇÃO TÉCNICA PELOS ESTABELECIMENTOS DA AGROPECUÁRIA PARAIBANA, EM 2017 29

ATRIBUTOS PESSOAIS DOS/AS RESPONSÁVEIS PELOS ESTABELECIMENTOS DA AGRICULTURA FAMILIAR NA PARAÍBA 31

DISTRIBUIÇÃO DOS RESPONSÁVEIS PELOS ESTABELECIMENTOS DA AGRICULTURA FAMILIAR DA PARAÍBA, POR SEXO 31

DISTRIBUIÇÃO DOS RESPONSÁVEIS PELOS ESTABELECIMENTOS DA AGRICULTURA FAMILIAR DA PARAÍBA, POR COR DA PELE 32

DISTRIBUIÇÃO DOS RESPONSÁVEIS PELOS ESTABELECIMENTOS DA AGRICULTURA FAMILIAR

DA PARAÍBA, POR FAIXA ETÁRIA 33

DISTRIBUIÇÃO DOS RESPONSÁVEIS PELOS ESTABELECIMENTOS DA AGRICULTURA FAMILIAR DA PARAÍBA, POR NÍVEL DE ESCOLARIDADE 34

DISTRIBUIÇÃO DOS RESPONSÁVEIS PELOS ESTABELECIMENTOS DA AGRICULTURA FAMILIAR PARAIBANA, EM RELAÇÃO À POSSE DA TERRA 35

PESSOAL OCUPADO NOS ESTABELECIMENTOS DA AGRICULTURA FAMILIAR NA PARAÍBA, EM 2017 37

CONSIDERAÇÕES FINAIS 39

APRESENTAÇÃO

Este trabalho foi elaborado pelo Observatório da Agricultura Familiar da Paraíba (OAF-PB), em parceria estabelecida entre o Governo do Estado, através da Secretaria de Estado do Planejamento, Orçamento e Gestão, com recursos do Fundo de Desenvolvimento do estado da Paraíba - FDE, Convênio FDE nº 002/2021, e o Departamento Intersindical de Estatística e Estudos Socioeconômicos (DIEESE), com a finalidade de contribuir para a estruturação de um instrumento de produção de informações, estudos e análises para o desenvolvimento da agricultura familiar paraibana.

O estudo está organizado em três seções: 1) esta pequena introdução; 2) uma seção sobre o "Perfil geográfico, demográfico e socioeconômica da Paraíba", com dados gerais do estado e dos seus 15 territórios rurais, como população, Produto Interno Bruto (PIB), benefícios previdenciários, Fundo de Participação dos Municípios (FPM) e distribuição dos estabelecimentos da agricultura familiar no estado; e 3) a terceira seção, denominada "Agricultura familiar no Nordeste e na Paraíba", elaborada com base no Censo Agropecuário de 2017, realizado pelo Instituto Brasileiro de Geografia e Estatística (IBGE), com informações detalhadas por territórios rurais e comentários com os destaques municipais. Entre os temas, "Valor e composição da produção agricultura familiar paraibana", com uma "radiografia" da produção de origem animal e vegetal; produtos comercializados pela agroindústria familiar; valor das despesas dos estabelecimentos por tipos; utilização de agrotóxicos; obtenção de orientação técnica; atributos pessoais dos/as responsáveis pelos estabelecimentos (sexo, cor da pele, idade, escolaridade e tipo de relação com a terra e pessoal ocupado nos estabelecimentos da agricultura familiar, como proprietários, concessionários ou assentados ainda sem titulação definitiva, arrendatários, parceiros, comodatários, ocupantes e produtores sem área.

PERFIL GEOGRÁFICO, DEMOGRÁFICO E SOCIOECONÔMICO DA PARAÍBA

O estado da Paraíba possui uma área de 56.467,242 km^2, com predomínio do bioma da Caatinga, em 97% do seu território. Esse bioma é exclusivamente brasileiro e caracterizado pela resistência de suas espécies de fauna e flora à seca. No litoral e nas regiões de planalto, ocorrem, ainda, formações vegetais de mangue e floresta tropical, como a Mata Atlântica.

O estado da Paraíba é dividido em 15 territórios rurais[1], que levam em conta programas já desenvolvidos que envolvam a agricultura familiar, além da dinâmica social, cultural logística e econômica historicamente estabelecidas.

Tabela 1 - *Distribuição dos biomas nos Territórios Rurais da Paraíba*

Territórios	Bioma	Área do Bioma (em ha)	% do Bioma no território
Mata Sul	Caatinga Mata Atlântica	458.036.771 2.024.848.631	18% 81%
Brejo	Caatinga	947.999.758	100%
Borborema	Caatinga Mata Atlântica	10.235.675.838 97.929.840	99% 1%
Curimataú	Caatinga	3.742.918.645	100%
Cariri	Caatinga	7.626.606.521	100%
Médio Sertão	Caatinga	5.830.193.023	100%
Vale de Piancó	Caatinga	5.557.726.716	100%
Médio Piranhas	Caatinga	2.859.333.353	100%
Alto Sertão	Caatinga	3.419.478.180	100%
Vale do Piranhas	Caatinga	2.179.760.675	100%
Serra do Teixeira	Caatinga	2.072.697.129	100%
Vale do Paraíba	Caatinga Mata Atlântica	1.826.421.406 665.577.745	73% 27%
Vale do Maringá	Caatinga	2.566.289.237	100%
Mata Norte	Caatinga Mata Atlântica	727.794.709 1.316.571.610	36% 64%
Piemonte da Borborema	Caatinga	2.307.820.129	100%

Fonte: IBGE Biomas - 2021

1. Nota Técnica nº 10, da Secretaria do Estado da Agricultura Familiar e de Desenvolvimento do Semiárido, de 31 de dezembro de 2020, que dispõe sobe a adequação dos Territórios Rurais Paraibanos alinhados as Regiões Geoadministrativas do Estado da Paraíba. Eles foram reorganizados em 2020 e já existiam anteriormente.

Segundo estimativas populacionais do IBGE, para 2021, a Paraíba tinha 4.059.905 habitantes em seus 223 municípios, sendo 967.013 (24%) residentes em áreas rurais. O maior contingente de população rural encontra-se no Território da Borborema, que conta com 38 municípios, onde residem 242.592 pessoas na área rural, 27% de toda a população do território. Em termos proporcionais, destaca-se o Território da Serra do Teixeira, com sete municípios, com 48% de sua população residindo na área rural.

Tabela 2 - *Estimativa da população rural e urbana nos Territórios Rurais da Paraíba - Julho de 2021*

Territórios	População do Território (TSE)	População Rural do Território (JUL-2021)*	
	Nº de habitantes	Nº de habitantes	%
Mata Sul	1.336.175	87.162	7%
Brejo	138.597	37.763	27%
Borborema	883.046	242.592	27%
Curimataú	108.692	41.776	38%
Cariri	116.819	44.909	38%
Médio Sertão	229.036	49.445	22%
Vale do Piancó	148.467	54.516	37%
Médio Piranhas	119.599	34.275	29%
Alto Sertão	178.797	69.159	39%
Vale do Piranhas	118.110	39.838	34%
Serra do Teixeira	85.509	41.444	48%
Vale do Paraíba	183.716	71.072	39%
Vale do Maringá	71.304	25.024	35%
Mata Norte	161.850	51.958	32%
Piemonte da Borborema	180.188	76.082	42%
Total	**4.059.905**	**967.013**	**24%**

Fontes: Tribunal Superior Eleitoral (TSE);
IBGE - Contas Nacionais - Estimativa da População Residente
(*) Cálculo da estimativa da população rural e urbana com base nos pesos do Censo
Populacional de 2010/IBGE, a partir das Estimativas da População Residente no Brasil (IBGE/julho de 2018).

A Tabela 3 traz informações sobre os benefícios previdenciários pagos em dezembro de 2020 em cada território (total e para beneficiários rurais); os valores pagos em 2020 (total e para beneficiários rurais); o valor dos repasses do Fundo de Participação dos Municípios (FPM); e a proporção dos benefícios pagos a beneficiários rurais em relação ao FPM. Os dados demonstram a importância desses recursos para a economia local - em especial para o comércio e os serviços - e como fonte de renda das famílias.

Em 14 dos 15 territórios rurais, o valor pago aos beneficiários rurais, em 2020, superou a marca de 50% do valor total dos benefícios. Em três territórios, o valor dos benefícios rurais foi igual ou superior a 80% do valor total dos benefícios: Médio Piranhas (80%), Curimataú (82%) e Serra do Teixeira (85%). Somente na Mata Sul, onde estão localizados os grandes centros urbanos da Paraíba, é que os benefícios rurais tiveram uma participação menor, de 13%, e onde os valores dos benefícios urbanos atingiram 87%. No

total do estado da Paraíba, os valores pagos a beneficiários rurais atingiram praticamente 50% do valor total dos benefícios (Tabela 3).

Tabela 3 – *Benefícios previdenciários pagos em dezembro de 2020, valor dos benefícios pagos no ano de 2020 (total e para população rural), repasses do Fundo de Participação dos Municípios – FPM em 2021 e proporção do valor dos benefícios rurais em relação ao FPM nos Territórios Rurais da Paraíba*

Município	Quantidade de beneficios previdenciários pagos (DEZ-2020)		Valor do beneficios pagos em 2020 (em R$)			FPM - Valor dos repasses em 2021 (em R$)	% Benef. Prev. Rurais/ repasses do FPM
	Total	Rural	Total	Rural	% Rural		
Mata Sul	151.551	26.807	2.537.570.021	328.098.177	13%	738.158.133	-56%
Brejo	23.331	14.919	311.949.823	184.656.094	59%	155.356.822	19%
Borborema	141.776	81.712	2.024.533.613	1.013.097.257	50%	1.129.432.502	-10%
Curimataú	19.772	16.727	250.595.088	204.604.732	82%	142.076.636	44%
Cariri	25.597	19.915	336.257.499	246.427.692	73%	234.842.322	5%
Médio Sertão	35.763	24.107	482.303.227	293.187.176	61%	306.024.173	-4%
Vale do Piancó	30.024	23.247	384.633.589	285.801.926	74%	245.884.782	16%
Médio Piranhas	26.147	21.947	334.593.185	267.505.397	80%	159.768.815	67%
Alto Sertão	36.968	28.435	476.771.616	346.526.573	73%	214.821.848	61%
Vale do Piranhas	22.707	16.211	304.663.954	198.872.030	65%	153.148.626	30%
Serra do Teixeira	15.419	13.488	196.545.007	166.530.537	85%	95.858.465	74%
Vale do Paraíba	28.732	20.413	373.231.005	249.967.681	67%	223.291.162	12%
Vale do Maringá	15.272	12.462	199.033.931	153.229.962	77%	103.997.706	47%
Mata Norte	26.018	15.363	343.212.782	187.363.882	55%	171.859.145	9%
Piemont da Borborema	35.797	29.034	464.497.804	358.983.466	77%	727.026.766	-51%
Total	**634.874**	**364.787**	**9.020.392.144**	**4.484.852.582**	**50%**	**4.801.547.905**	**-7%**

Fontes: Dados Abertos da Previdência Social - Estatísticas por Município; Tesouro Nacional - Relatório de Transferências Nacionais
Elaboração: DIEESE

Os recursos transferidos via Previdência Rural representaram 93% do valor total do Fundo de Participação dos Municípios (Tabela 3). Em 11 territórios, os valores da Previdência Rural superaram as transferências recebidas do Fundo Participação dos Munícipios (FPM), como é o caso do Território de Serra do Teixeira, onde os recursos previdenciários rurais foram 74% superiores às transferências do FPM. Por outro lado, a Mata Sul (44%) e o Piemonte da Borborema (49%) foram os únicos territórios em que os recursos da Previdência Rural representaram menos da metade do valor do FPM. Isso se deve, principalmente, por serem regiões mais urbanizadas. No território de Borborema, o valor dos benefícios da Previdência Rural foi 10% inferior ao valor das transferências do FPM e, no Médio Sertão, apenas 4% menor.

Quando se consideram os recursos previdenciários totais (urbanos + rurais), em 14 territórios os valores previdenciários superam o valor dos repasses do FPM, à exceção de Piemonte da Borborema, onde o valor do FPM é 57% maior.

O Produto Interno Bruto (PIB) da Paraíba foi de cerca de R$ 68 bilhões, em 2019, segundo dados das Contas Nacionais do IBGE. Esse valor representava 0,9% do PIB nacional e 6,5% do PIB do Nordeste (Tabela 4). O setor com a maior participação foi o de Serviços, com cerca de R$ 29 bilhões (42% do PIB estadual), seguido da administração, com R$ 20 bilhões (29%).

O setor agropecuário representava apenas pouco mais de 3% do PIB estadual, alcançando R$ 2,2 bilhões. No Território do Vale do Paraíba, com um PIB total de cerca de R$ 2 bilhões, o setor agropecuário tinha 12% de participação, a maior do setor entre todos os territórios.

Tabela 4 - *Produto Interno Bruto (PIB) total e PIB Setorial nos Territórios Rurais da Paraíba - 2019*

Territórios	PIB TerritoriaL 2019* (Mil R$)						% do PIB Agro/ Total
	Total	Agropecuário	Indústria	Serviços	Administração	Impostos	
Mata Sul	32.351.170	331.845	5.017.489	15.880.732	6.428.239	4.692.865	1%
Brejo	1.794.875	109.905	227.834	626.843	677.220	153.072	6%
Borborema	14.363.793	580.791	2.388.284	5.653.555	4.276.436	1.464.728	4%
Curimataú	999.982	58.991	48.369	273.656	568.175	50.792	6%
Cariri	1.421.396	84.718	77.589	554.948	630.640	73.502	6%
Médio Sertão	3.141.784	86.316	337.130	1.312.405	1.145.600	260.333	3%
Vale do Piancó	1.437.836	101.831	82.470	417.586	758.192	77.757	7%
Médio Piranhas	1.408.575	53.131	121.788	517.254	599.150	117.252	4%
Alto Sertão	2.265.734	73.618	159.254	917.165	899.407	216.290	3%
Vale do Piranhas	1.664.189	48.363	182.827	693.728	558.196	181.075	3%
Serra do Teixeira	718.480	67.731	35.198	177.155	405.275	33.120	9%
Vale do Paraíba	1.979.249	234.941	197.145	501.375	936.591	109.197	12%
Vale do Maringá	802.491	50.814	57.235	271.575	369.205	53.661	6%
Mata Norte	1.946.357	166.007	236.370	589.542	823.642	130.797	9%
Piemonte da Borborema	1.690.161	146.699	86.727	465.958	896.364	94.413	9%
Total	**67.986.074**	**2.195.702**	**9.255.709**	**28.853.476**	**19.972.331**	**7.708.855**	**3%**

Fontes: IBGE - Contas Nacionais - Estimativa da População Residente - PIB dos Municípios;
*PIB Total, para os grandes setores o valor representa o Valor Adicionado Bruto.
Elaboração: DIEESE

Os cinco municípios com maior PIB agropecuário na Paraíba, em 2019, foram Pedras de Fogo, Alagoa Nova, Santa Rita, Pocinhos e Bananeiras (Tabela 5). O município de Barra de São Miguel apresentou a maior participação do PIB agropecuário em relação ao PIB total do município (31%). Na sequência, Alagoa Nova (30%), São Miguel de Taipu (29%), Pocinhos (28%) e Matinhas (27%) completavam os cinco municípios que apresentaram as maiores participações do PIB agropecuário em relação ao PIB total do munícipio.

Tabela 5 - *Municípios paraibanos com os maiores PIBs agropecuários e maiores participações do PIB agropecuário no PIB total municipal*

Município	PIB municipal 2019**		% do PIB Agropecuário sobre o PIB Total
	Total	Agropecuário	
Pedras de Fogo	414.847.577	**105.584.137**	25%
Alagoa Nova	325.902.275	**98.770.901**	30%
Santa Rita	2.570.700.659	**85.264.397**	3%
Pocinhos	242.625.596	**68.283.020**	28%
Bananeiras	234.461.674	**43.989.121**	19%
Barra de São Miguel	65.229.226	20.356.875	**31%**
São Miguel de Taipu	68.365.664	19.670.582	**29%**
Matinhas	49.293.590	13.086.656	**27%**

Fontes: IBGE - Contas Nacionais – PIB dos Municípios – Estatísticas por municípios
*PIB Total, para os grandes setores o valor representa o Valor Adicionado Bruto.
Elaboração: DIEESE

AGRICULTURA FAMILIAR NO NORDESTE E NA PARAÍBA

DADOS GERAIS

Em 2017, a região Nordeste concentrava 47,2%do total de estabelecimentos da agricultura familiar no Brasil, somando 1,8 milhão de unidades produtivas.

Na região Nordeste, a Paraíba participava com 6,8% dos estabelecimentos da agropecuária familiar. A Bahia tinha a maior participação relativa no Nordeste, com 32,3% dos estabelecimentos familiares em seu território (Mapa 1).

Mapa 1 - *Distribuição dos estabelecimentos da Agricultura Familiar*
Região Nordeste - 2017

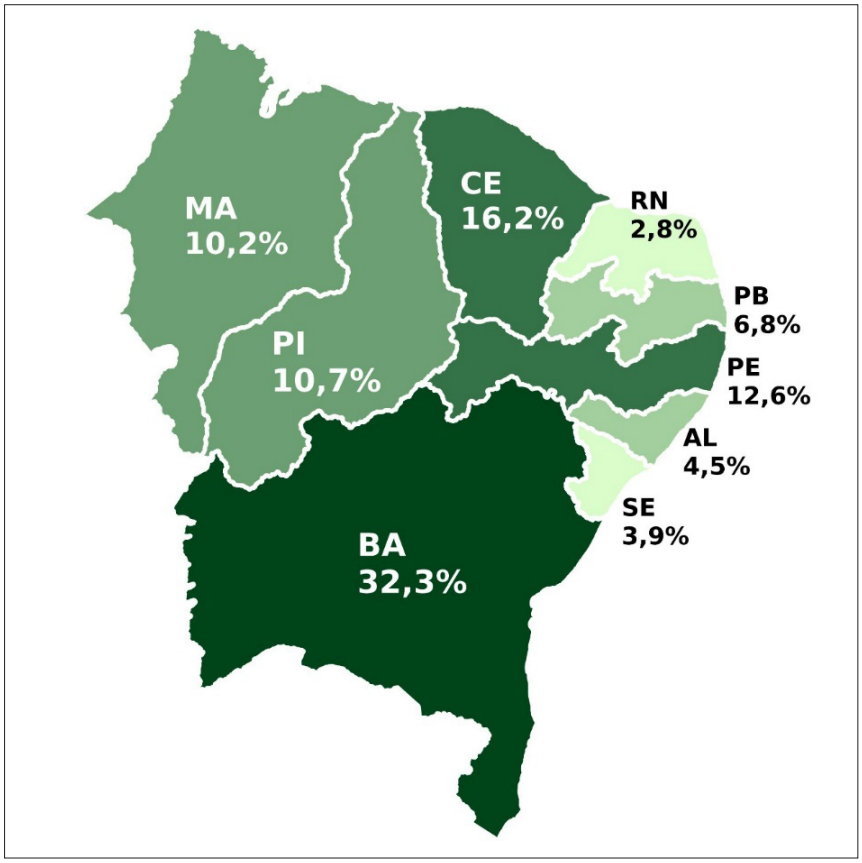

Fonte: Censo Agropecuário IBGE, 2017
Elaboração: DIEESE

Segundo dados do Censo Agropecuário de 2017, eram 125.489 os estabelecimentos da agricultura familiar na Paraíba, representando 77% do total dos estabelecimentos agropecuários do estado.

O elevado número de estabelecimentos indica a importância da agricultura familiar para a dinâmica econômica da produção rural paraibana e para subsistência das famílias envolvidas nesse modelo de produção, considerando-se a renda oriunda da atividade econômica do empreendimento familiar, assim como a produção para autoconsumo (Gráfico 1).

Gráfico 1 - *Distribuição dos estabelecimentos agropecuários por tipo*
Paraíba - 2017

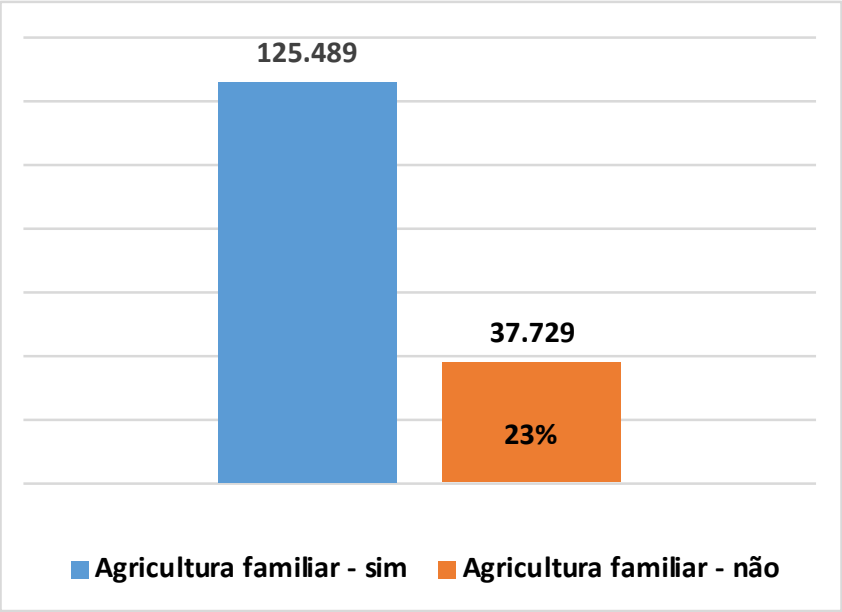

Fonte: Censo Agropecuário 2017-IBGE
Elaboração: DIEESE

Os estabelecimentos da agricultura familiar estavam mais presentes nos municípios que compõem o Território da Serra do Teixeira, localizado na região nordeste do estado. Esse território é composto por 7 municípios que têm, em média, 85% de participação de estabelecimentos da agricultura familiar entre todos os estabelecimentos agropecuários (Tabela 6).

A menor presença relativa de estabelecimentos da agricultura familiar (72%) se dá no Território da Borborema, embora, em termos absolutos, seja o território com maior número de estabelecimentos familiares (mais de 30 mil). É também na Borborema onde se localiza o município de Natuba, com a maior participação da agropecuária familiar, que responde por 95% de todos os estabelecimentos agropecuários do munícipio. Na Borborema também está o maior número de agricultores não familiares (11.524), e é onde se localizam os dois municípios onde apareceram as menores participações de agricultura familiar no total dos estabelecimentos agropecuários da Paraíba: Riacho de Santo Antônio, com 43%, e Boa Vista, com 46% (Tabela 6).

Tabela 6 - *Número de estabelecimentos agropecuários na Paraíba, por Território Rural por tipos de agricultor - 2017*

Território	Agricultura familiar - não	Agricultura familiar - sim	Total	% de agricultores familiares
Mata Sul	2.465	7.450	9.915	75%
Brejo	1.906	5.425	7.331	74%
Borborema	11.561	30.137	41.698	72%
Curimataú	2.163	6.942	9.105	76%
Cariri	2.785	8.173	10.958	75%
Médio Sertão	1.933	6.680	8.613	78%
Vale do Piancó	2.473	9.378	11.851	79%
Médio Piranhas	756	2.809	3.565	79%
Alto Sertão	1.835	8.148	9.983	82%
Vale do Piranhas	979	4.458	5.437	82%
Serra do Teixeira	1.182	6.451	7.633	85%
Vale do Paraíba	2.557	9.200	11.757	78%
Vale do Maringá	1.019	2.937	3.956	74%
Mata Norte	1.920	6.283	8.203	77%
Piemont da Borborema	2.195	11.018	13.213	83%
Total	**37.729**	**125.489**	**163.218**	**77%**

Fonte: Censo Agropecuário/IBGE, 2017
Elaboração: DIEESE

Os estabelecimentos da agricultura familiar na Paraíba se concentravam nas áreas até 10 hectares (70,8% deles), sendo que 12,6% tinham área inferior a 1 ha e 16,3% tinham entre 1 e 2 hectares (Tabela 7). Com áreas de até 20 hectares, estavam 84% de todos os estabelecimentos da agricultura familiar.

Tabela 7 - *Número de estabelecimentos agropecuários, por tipos e grupos de área Paraíba - 2017*

Grupos de área total	Estabelecimentos familiares		Estabelecimentos não familiares		Total
	Por faixa de área	% do total	Por faixa de área	% do total	
Mais de 0 a menos de 0,5 ha	**7.032**	5,6%	**3.263**	**8,6%**	10.295
De 0,5 a menos de 1 ha	8.787	7,0%	3.248	8,6%	12.035
De 1 a menos de 2 ha	20.441	16,3%	6.556	17,4%	26.997
De 2 a menos de 3 ha	14.286	11,4%	3.764	10,0%	18.050
De 3 a menos de 5 ha	17.484	13,9%	3.802	10,1%	21.286
De 5 a menos de 10 ha	20.871	16,6%	4.364	11,6%	25.235
De 10 a menos de 20 ha	16.542	13,2%	3.565	9,4%	20.107
De 20 a menos de 50 ha	12.758	10,2%	2.967	7,9%	15.725
De 50 a menos de 200 ha	6.025	4,8%	2.915	7,7%	8.940
De 200 a menos de 1000 ha	237	0,2%	2.497	6,6%	2.734
De 1.000 ha e mais	-		252	0,7%	252
Produtor sem área	1.026	0,8%	536	1,4%	1.562
Total	**125.489**	**100,0%**	**37.729**	**100,0%**	**163.218**

Fonte: Censo Agropecuário IBGE, 2017
Elaboração: DIEESE

A Tabela 8, a seguir, traz dados da dedicação dos estabelecimentos da agricultura familiar à produção animal e vegetal nos territórios rurais da Paraíba. Observa-se que 71,7% dos 125.489 estabelecimentos da agricultura familiar da Paraíba se dedicavam à produção de origem animal e 83,6% deles à produção de origem vegetal.

Quanto aos territórios, 92,5% dos estabelecimentos da agricultura familiar no território do Médio Piranhas estavam dedicados à produção animal e, no Vale do Maringá, 91,5%. No município de Riacho de Santo Antônio, 100% dos estabelecimentos estavam dedicados à produção animal e, em Alcantil, 99,7%, ambos na Borborema.

Os territórios rurais com maior porcentagem de estabelecimentos familiares dedicados à produção vegetal eram a Mata Sul (94,1%); o Vale do Paraíba, com 93,7%, Piemonte da Borborema, com 92,9% e Serra do Teixeira, com 92,8%. Dez municípios têm mais de 98% de seus estabelecimentos com produção vegetal: Areial, Esperança, Montadas e São Sebastiao da Lagoa Grande, na Serra da Borborema; Cacimbas e Teixeira, no Médio Sertão, e Cacimba de Dentro; Cassengue, Damião e Pilões, no Piemonte da Borborema

Tabela 8 – *Número de estabelecimentos da agricultura familiar paraibana nos Territórios Rurais por dedicação à produção de origem animal e vegetal - 2017*

Territórios	Dedicados à Produção de origem animal	Dedicados à Produção de origem vegetal	Total de estabelecimentos da agropecuária familiar	% de estab. dedicados à produção animal	% de estab. dedicados à produção vegetal
Mata Sul	2.917	7.014	7.450	39,2%	94,1%
Brejo	3.557	4.683	5.425	65,6%	86,3%
Borborema	23.142	24.652	30.137	76,8%	81,8%
Curimataú	5.582	5.422	6.942	80,4%	78,1%
Cariri	6.765	3.780	8.173	82,8%	46,2%
Médio Sertão	5.211	5.727	6.680	78,0%	85,7%
Vale do Piancó	8.082	8.101	9.378	86,2%	86,4%
Médio Piranhas	2.599	2.269	2.809	92,5%	80,8%
Vale do Piranhas	3.425	3.718	4.458	76,8%	83,4%
Serra do Teixeira	5.021	5.984	6.451	77,8%	92,8%
Vale do Paraíba	4.142	8.620	9.200	45,0%	93,7%
Vale do Maringá	2.687	1.716	2.937	91,5%	58,4%
Mata Norte	2.668	5.706	6.283	42,5%	90,8%
Piemonte da Borborema	7.416	10.238	11.018	67,3%	92,9%
Total	**90.000**	**104.849**	**125.489**	**71,7%**	**83,6%**

Fonte: Censo Agropecuário/IBGE, 2017
Elaboração: DIEESE
* A soma das atividades impossibilita a totalização dos estabelecimentos por município e território.

A Tabela 9, a seguir, mostra a renda total obtida pelos estabelecimentos da agricultura familiar, em cada

Território, que totalizou R$ 2,27 bilhões, de acordo com o Censo Agropecuário de 2017. O Território da Borborema teve a maior contribuição, com R$ 606,6 milhões (26,7% do total).

Tabela 9 - *Renda obtida pelos estabelecimentos da agricultura familiar paraibana, por Território Rural (em mil reais)- 2017*

Territórios	Total	Participação %
Mata Sul	152.437	6,7%
Brejo	107.933	4,8%
Borborema	606.562	26,7%
Curimataú	107.196	4,7%
Cariri	149.955	6,6%
Médio Sertão	120.581	5,3%
Vale do Piancó	149.267	6,6%
Médio Piranhas	66.868	2,9%
Alto Sertão	155.286	6,8%
Vale do Piranhas	75.509	3,3%
Serra do Teixeira	89.319	3,9%
Vale do Paraíba	135.661	6,0%
Vale do Maringá	71.655	3,2%
Mata Norte	117.223	5,2%
Piemont da Borborema	166.364	7,3%
Total	**2.271.816**	**100,0%**

Fonte: Censo Agropecuário/IBGE, 2017

Essa renda obtida pelos estabelecimentos da agricultura familiar na Paraíba é dividida em três tipos: a) receitas do estabelecimento com produção agropecuária; b) outras receitas do estabelecimento (desinvestimento, serviço de turismo rural, exploração mineral, atividade de artesanato, tecelagem etc. e demais receitas do estabelecimento); e c) outras receitas do produtor (aposentadorias e pensões; renda de atividades desenvolvidas fora do estabelecimento; renda proveniente de programas dos governos).

Os dados apresentados na Tabela 10, a seguir, demonstram que, em 2017, a principal fonte de receita dos estabelecimentos da agricultura familiar foram os "Recursos de aposentadorias ou pensões", que alcançaram a cifra de R$ 1,155 bilhão, o equivalente a 51% do total de R$ 2,272 bilhões de todas as receitas. Esse resultado dá a dimensão da importância dessa fonte de renda para os/as agropecuaristas familiares.

A segunda maior fonte foram as "Receitas da produção dos estabelecimentos", na ordem de R$ 861,6 milhões (37,9% do total das receitas), com destaque para a produção de "Animais e seus produtos", com uma receita de R$ 518 milhões.

Tabela 10 – *Origem dos rendimentos dos/as agropecuaristas familiares da Paraíba em 2017 (em mil reais)*

Receitas da produção do estabelecimento	**861.594 (37,9%)**
Produtos vegetais	265.319
Animais e seus produtos	517.808
Produtos da agroindústria	78.468
Outras receitas do estabelecimento	**44.743 (2,0%)**
Desinvestimentos	12.334
Serviço de turismo rural	178
Exploração mineral	599
Atividade de artesanato, tecelagem etc.	2.170
Demais receitas do estabelecimento	29.462
Outras receitas do/a produtor familiar	**1.365.485 (60,1%)**
Recursos de aposentadorias ou pensões	1.155.172
Rendas obtidas em atividades fora do estabelecimento	78.411
Recebimento de prêmio de Programa Garantia Safra	15.661
Recebimento de prêmio de Programa Garantia da Atividade Agropecuária da Agricultura Familiar - PROAGRO Mais	352
Recebimento do Programa Nacional de Habitação Rural Minha Casa Minha Vida	1.215
Recebimento de pagamento por serviços ambientais (Bolsa Verde e Programas Estaduais)	598
Receitas provenientes de programas dos Governos (federal, estadual ou municipal)	114.075
Total	**2.271.822 (100,0%)**

Fonte: Censo Agropecuário IBGE, 2017
Elaboração: DIEESE

VALOR E COMPOSIÇÃO DA PRODUÇÃO AGRICULTURA FAMILIAR PARAIBANA, EM 2017

Em 2017, os estabelecimentos da agricultura familiar representaram 76,9% do total dos estabelecimentos agropecuários da Paraíba e foram responsáveis por quase a metade (47,8%) do valor da produção agropecuária paraibana, com um resultado de R$ 1,076 bilhão (Gráfico 2).

A Tabela 11, a seguir, traz os mesmos dados do Gráfico 2, estratificados por cada território. Observa-se que o Território da Borborema – que tem o maior número de municípios, 38 - foi o que apresentou os maiores valores da produção agricultura familiar (R$ 288,5 milhões, ou 27% do valor total da agricultura familiar no estado), seguido de longe pelo Território da Mata Sul, com 95,6 milhões (8,9% do valor total).

A participação da agricultura familiar no total da produção agropecuária paraibana foi de 48%, variando de 23%, no Território da Mata Sul e no Território da Mata Norte, a 76%, no Território do Alto Sertão.

Gráfico 2 - *Valor da Produção Agropecuária na Paraíba, por tipo de estabelecimento (em mil reais) - 2017*

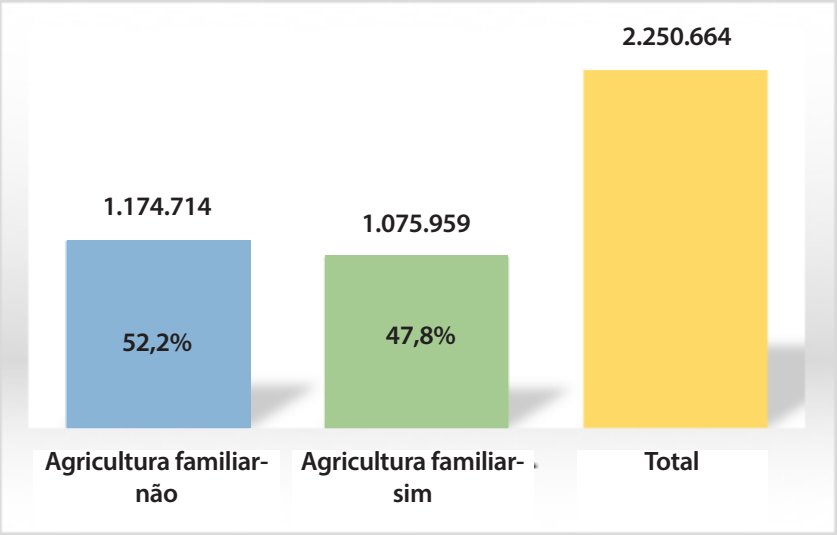

Fonte: Censo Agropecuário IBGE, 2017
Elaboração: DIEESE

Tabela 11 - *Valor total da produção agropecuária na Paraíba por Território Rural e tipos de estabelecimentos (em mil reais)- 2017*

Territórios	Valor da produção da agricultura familiar	Valor da produção da agricultura não familiar	Valor total da produção agropecuária	% da agropecuária familiar
Mata Sul	95.635,00	327.532,00	423.166,00	23%
Brejo	55.223,00	56.917,00	112.138,00	49%
Borborema	288.470,00	188.037,00	476.503,00	61%
Curimataú	41.689,00	20.568,00	62.257,00	67%
Cariri	60.200,00	32.788,00	92.992,00	65%
Médio Sertão	58.519,00	30.473,00	88.989,00	66%
Vale do Piancó	75.180,00	26.764,00	101.944,00	74%
Médio Piranhas	38.214,00	27.392,00	65.606,00	58%
Alto Sertão	69.696,00	22.318,00	92.014,00	76%
Vale do Piranhas	31.207,00	18.469,00	49.673,00	63%
Serra do Teixeira	30.914,00	29.155,00	60.070,00	51%
Vale do Paraíba	62.616,00	119.315,00	181.933,00	34%
Vale do Maringá	34.510,00	22.508,00	57.017,00	61%
Mata Norte	66.842,00	222.717,00	289.558,00	23%
Piemonte da Borborema	67.044,00	29.761,00	96.804,00	69%
Total	**1.075.959,00**	**1.174.714,00**	**2.250.664,00**	**48%**

Fonte: Censo Agropecuário/IBGE, 2017
Elaboração: DIEESE

A Tabela 12, a seguir, traz os valores da produção agricultura familiar na Paraíba, em 2017, segundo a origem dos produtos (animal ou vegetal) em cada território e a participação de cada segmento no valor total.

Se, para o estado como um todo, o valor total da produção agricultura familiar foi de R$ 1,076 bilhão, o valor da produção familiar de origem animal foi de R$ 649,7 milhões (60,5% do total) e o valor da produção de origem vegetal foi de R$ 423,9 milhões (39,5% do total).

Os territórios com maior participação da produção de origem animal foram: Vale do Maringá (92,7% do valor total agropecuário); Médio Piranhas (88,9%); Cariri (82,0%); e Alto Sertão (81,9%). Dos municípios, os destaques eram de Riacho de Santo Antônio, com 100% do valor de produção originado da produção animal, e Alcantil, com 99,2%, ambos na Borborema. E em Cajazeirinhas, no Vale do Maringá, com 99,5%. Sessenta e oito municípios têm mais de 80% do valor de produção na origem animal.

Os territórios com maior participação da produção de origem vegetal foram: Mata Sul, com 81,2% de seu valor obtido na produção vegetal; a Mata Norte com 79,1% e o Vale do Paraíba, com 60,4%. Entre os municípios, os destaques eram Pitimbu, com 97,8% do valor total agropecuário originário na produção de origem vegetal; Santa Rita, com 96,5%; e Caaporã, com 95,4%, os três na Mata Sul. Dezenove municípios tinha mais de 80% do valor da produção de origem vegetal.

Tabela 12 - *Composição do valor da produção agricultura familiar na Paraíba, conforme a origem dos produtos, por Território Rural (em mil reais) - 2017*

Territórios	Produção de origem animal	Produção de origem vegetal	Valor total	Animal	Vegetal
Mata Sul (*)	17.918,00	77.503,00	95.421,00	18,8%	81,2%
Brejo	25.136,00	30.086,00	55.222,00	45,5%	54,5%
Borborema	186.993,00	101.479,00	288.472,00	64,8%	35,2%
Curimataú	27.030,00	14.659,00	41.689,00	64,8%	35,2%
Cariri (**)	48.006,00	10.513,00	58.519,00	82,0%	18,0%
Médio Sertão	44.484,00	14.031,00	58.515,00	76,0%	24,0%
Vale de Piancó	55.154,00	20.026,00	75.180,00	73,4%	26,6%
Médio Piranhas	33.957,00	4.256,00	38.213,00	88,9%	11,1%
Alto Sertão	57.063,00	12.635,00	69.698,00	81,9%	18,1%
Vale do Piranhas	24.818,00	6.388,00	31.206,00	79,5%	20,5%
Serra do Teixeira	21.268,00	9.646,00	30.914,00	68,8%	31,2%
Vale do Paraíba	24.782,00	37.835,00	62.617,00	39,6%	60,4%
Vale do Maringá	31.979,00	2.533,00	34.512,00	92,7%	7,3%
Mata Norte (***)	13.838,00	52.478,00	66.316,00	20,9%	79,1%
Piemonte da Borborema	37.225,00	29.820,00	67.045,00	55,5%	44,5%
Total (****)	**649.651,00**	**423.888,00**	**1.075.959,00**	**60,5%**	**39,5%**

Fonte: Censo Agropecuário IBGE, 2017. Elaboração: DIEESE
(*) – O valor da produção animal e vegetal do município de Cabedelo não pôde ser publicado, para não identificar o produtor.
(**) – O valor da produção vegetal do município de Caraúbas não pôde ser publicado, para não identificar o produtor.
(***) – O valor da produção animal e vegetal do município de Capim não pôde ser publicado, para não identificar o produtor.
(****) – O valor total é R$ 2,42 milhões superior à soma das duas primeiras colunas, por conta dos valores que não puderam ser publicados, para não identificar o produtor.

Os maiores valores de produção, animal e vegetal, foram encontrados nos municípios de Pedras do Fogo, no Vale do Paraíba, com R$ 24,927 milhões, sendo 19,1% oriundos da produção animal e 80,9% oriundos da produção vegetal; e Queimadas, na Borborema, que obteve um valor bruto da produção de R$ 20,1 milhões, sendo 83% oriundos da produção animal e 17% da produção vegetal.

RADIOGRAFIA DA PRODUÇÃO DE ORIGEM ANIMAL NOS ESTABELECIMENTOS DA AGRICULTURA FAMILIAR NA PARAÍBA, EM 2017

Os itens 1 e 2, a seguir, detalham aspectos da produção de origem animal nos estabelecimentos da agricultura familiar na Paraíba.

1. Dedicação dos estabelecimentos

A produção de origem animal nos estabelecimentos da agricultura familiar na Paraíba se concentrava, principalmente, na criação de aves, com 54,1% dos estabelecimentos dedicados a essa atividade. Destacavam-se os Territórios do Vale do Piancó, com 68,2% e Alto Sertão, com 68,1% (Tabela 13). Os municípios com destaque nessa criação eram: Alcantil (89,5%), Santa Cecilia (87,2%), e Umbuzeiro (86,2%), todos da Borborema, além de Santa Inês (88%), no Vale do Piancó.

A proporção de estabelecimentos dedicados à criação de animais de pequeno porte[2] é pequena (0,5%), atingindo 1,1% na Mata Norte e 1% no Médio Piranha. O município de Marizópolis, no Vale do Piranhas, destaca-se com 4,4% dos estabelecimentos da agricultura familiar envolvidos com essas criações. Jacaraúna, na Mata Norte, aparece com 3,7% e Alagoa Nova, na Borborema, com 3,2%.

A criação de animais de médio porte[3] estava presente em 23,4% dos estabelecimentos da agropecuária familiar, com destaque para os territórios do Cariri, com 46,9%, e Curimataú, com 34,6%. Entre os municípios, destacavam-se Riacho de Santo Antônio, com 86,4%, Barra de São Miguel e São Domingo do Cariri, com 75,7%, os três da Borborema.

Na criação de animais de grande porte[4], estavam envolvidos 38,6% dos estabelecimentos da agropecuária familiar. Os territórios com maior participação nessa atividade eram o Médio Piranhas, com 74,3% dos estabelecimentos, e o Vale do Maringá, com 69,2% (Tabela 13). Entre os municípios se destacavam São José do Brejo da Cruz, com 89,8%; Brejo da Cruz, com 86,2%; e São Bento, com 85,6%, todos no Território do Médio Piranhas. Destaque também para Paulista, com 85,2%, no Território do Vale do Maringá.

2. Coelhos, da apicultura, da sericicultura e da aquicultura.
3. Suínos, caprinos e ovinos.
4. Bovinos, bubalinos, equinos, asininos e muares.

Tabela 13 – *Participação dos estabelecimentos da agricultura familiar por tipo de criação animal (%), por Território Rural - 2017*

Territórios	Criação de pequenos animais	Criação de aves	Criação de animais de médio porte	Criação de animais de grande porte
Mata Sul	0,6%	29,1%	5,7%	14,7%
Brejo	0,8%	43,5%	15,2%	35,2%
Borborema	0,4%	62,4%	29,7%	39,0%
Curimataú	0,3%	62,2%	34,6%	44,9%
Cariri	0,1%	55,1%	46,9%	40,6%
Médio Sertão	0,2%	57,7%	29,5%	42,7%
Vale do Piancó	0,4%	68,2%	22,6%	52,2%
Médio Piranhas	1,0%	62,8%	27,0%	74,3%
Alto Sertão	0,7%	68,1%	21,4%	45,1%
Vale do Piranhas	0,5%	51,0%	17,7%	51,2%
Serra do Teixeira	0,2%	62,4%	22,3%	36,5%
Vale do Paraíba	0,5%	32,8%	10,1%	20,2%
Vale do Maringá	0,5%	63,1%	23,1%	69,2%
Mata Norte	1,1%	26,8%	6,5%	19,8%
Piemonte da Borborema	0,8%	48,0%	19,5%	36,2%
Total	**0,5%**	**54,1%**	**23,4%**	**38,6%**

Fonte: Censo Agropecuário/IBGE, 2017
Elaboração: DIEESE
(*) O mesmo estabelecimento pode ter mais de uma atividade. O total não precisa ser 100%.

2. Valor da produção de origem animal, por tipos

Quanto ao valor da produção animal, o Território da Borborema se destacava em todos os tipos de criação, com exceção dos pequenos animais, em que os valores da produção do Piemonte da Borborema, Vale do Paraíba, e Mata Norte eram superiores aos demais (Tabela 14).

No valor da produção de pequenos animais (R$ 3,4 milhões), destacavam-se os Territórios do Vale do Paraíba, com R$ 795 mil (23,4% do valor total); e o Piemonte da Borborema com R$ 761 mil (22,4%). O município de Bananeiras, no Piemonte da Borborema, apresentou um valor de produção na ordem de R$ 703 mil (20,7% do total); Itatuba, no Vale do Paraíba, teve um valor de produção de R$ 627 mil (18,5%); e Marcação, na Mata Norte, de R$ 615 mil (18,1%).

No valor da produção de aves (R$ 99,7 milhões), destacavam-se os Territórios da Borborema, com R$36,1 milhões (36,2% do total); Alto Serão com R$ 10,2 milhões (10,1%); e Médio Sertão, com R$ 10,1 milhões (também 10,1%). Os municípios de Queimadas, com R$ 6,2 milhões (6,2% do valor total); e Soledade, com R$ 4,3 milhões (4,3%), se destacavam na região da Borborema. Também Uiraúna, no Alto Sertão, apresentou um alto valor de produção de aves, com R$ 5,3 milhões (5,3%).

No valor da produção de animais de médio porte (R$ 54,2 milhões), destacavam-se os Territórios da Borborema, com R$ 15,1 milhões (27,8% do total) e do Cariri, com R$ 14,8 milhões (27,3%). Destaque para os municípios de Monteiro, com R$ 3,7 milhões (6,9% do valor total) e Sumé, com 2,2 milhões (4,1%), ambos no Cariri; e de Gado Bravo, com R$ 1,5 milhão (2,8%).

O maior valor da produção animal foi verificado na produção de animais de grande porte (R$ 436,9 milhões), com destaque para o Territórios da Borborema, com R$ 104,4 milhões (23,9% do valor total); seguido de longe pelo Vale do Piancó, com R$ 45,7 milhões (10,5%). Entre os municípios, Barra de Santana aparecia com o maior valor declarado na produção de animais de grande porte, com R$ 13,5 milhões (3,1% do valor total), seguido por Gado Bravo, com R$ 11,7 milhões (2,7%), ambas cidades na Borborema. Pombal, no Vale do Maringá, também se destacou, com R$ 10,4 milhões (2,4%).

***Tabela 14** - Valor da produção animal em estabelecimentos da agricultura familiar por tipo de criação, por Território Rural (em mil reais) - 2017*

Territórios	Criação de pequenos animais	Criação de Aves	Criação de animais de médio porte	Criação de animais de grande porte
Mata Sul	395,00	3.266,00	522,00	13.130,00
Brejo	257,00	2.967,00	1.582,00	18.966,00
Borborema	201,00	36.083,00	15.074,00	104.374,00
Curimataú	17,00	5.248,00	2.772,00	17.501,00
Cariri	0,00	6.313,00	14.815,00	22.875,00
Médio Sertão	0,00	10.087,00	3.555,00	29.279,00
Vale do Piancó	123,00	4.577,00	2.498,00	45.655,00
Médio Piranhas	54,00	2.825,00	1.148,00	27.639,00
Alto Sertão	39,00	10.423,00	3.597,00	41.726,00
Vale do Piranhas	56,00	1.793,00	1.901,00	20.648,00
Serra do Teixeira	12,00	2.049,00	1.135,00	13.701,00
Vale do Paraíba	795,00	5.450,00	1.524,00	16.622,00
Vale do Maringá	44,00	1.806,00	1.589,00	28.284,00
Mata Norte	642,00	2.257,00	70,00	8.222,00
Piemonte da Borborema	761,00	4.576,00	2.466,00	28.233,00
Total	**3.396,00**	**99.720,00**	**54.248,00**	**436.855,00**

Fonte: Censo Agropecuário/IBGE, 2017
OBS: Como os dados foram desagregados por municípios, em alguns o valor é inibido para não identificar o informante. EX: Determinado município só possui uma propriedade produtora de algodão, logo o valor de sua produção (ou algum outro dado) deve ser inibido. Assim, alguns subtotais podem não bater na soma ou não constar no resultado.
Elaboração: DIEESE

RADIOGRAFIA DA PRODUÇÃO DE ORIGEM VEGETAL NOS ESTABELECIMENTOS DA AGRICULTURA FAMILIAR NA PARAÍBA, EM 2017

Os itens 1 a 6, a seguir, detalham informações sobre cada tipo de produção de origem vegetal da agricultura familiar paraibana.

1. Lavouras temporárias

Segundo o Censo Agropecuário de 2017, 98.870 estabelecimentos (78,8% do total de 125.489 estabelecimentos da agricultura familiar do estado) se dedicavam à produção vegetal de lavouras temporárias. Nesses 98.870 estabelecimentos, a maior presença foi registrada no Território da Borborema - o maior da Paraíba, com 38 municípios -, onde 22.845 estabelecimentos (23,1% do total), cultivavam esse tipo de lavoura (Tabela 15). Na sequência, aparecia, em um distante segundo lugar, o Território do Piemonte da Borborema, com 9.573 estabelecimentos (9,7% do total).

Entre os municípios que cultivam lavouras temporárias, destaque para Queimadas, onde 1.959 estabelecimentos (92,9% dos estabelecimentos da agricultura familiar do município) se dedicavam à lavoura temporária, seguido por Aroeiras, onde 1.639 estabelecimentos (94,6% do total de estabelecimentos da agricultura familiar do município) plantavam esse tipo de lavoura, ambos na Borborema. Também em Monteiro, no Cariri, 1.784 estabelecimentos (76,0% do total de estabelecimentos da agricultura familiar do município) cultivavam lavouras temporárias.

2. Lavouras permanentes

As lavouras permanentes estavam presentes em 11.840 estabelecimentos (9,4% dos 125.489 estabelecimentos da agricultura familiar do estado). Entre esses 11.840 estabelecimentos, o destaque também ficou com o Território da Borborema, onde 3.496 estabelecimentos (29,5% do total), produziam lavouras permanentes (Tabela 15). O Território do Piemonte da Borborema tinha 1.888 estabelecimentos (15,9% do total) e o Território da Mata Sul tinha 1.871 estabelecimentos (15,8%).

Entre os municípios que cultivam lavouras permanentes, o destaque foi Alagoa Nova, na Borborema, com 926 estabelecimentos (72% dos estabelecimentos da agricultura familiar do município) cultivavam lavouras permanentes; e Pitimbu, na Mata Sul, onde 509 estabelecimentos (60% do total do município) estavam produzindo lavouras permanentes.

3. Horticultura

A Horticultura estava presente em 11.020 estabelecimentos (8,8% dos 125.489 estabelecimentos da agricultura familiar no estado). Entre esses 11.020 estabelecimentos com produção de hortaliças, legumes e frutas, destacou-se o Território da Mata Sul, com 3.110 estabelecimentos (28,2% do total), e o Território da Borborema, com 2.179 (19,8%) (Tabela 15).

Entre os municípios horticultores, os destaques ficaram com Lagoa Seca, na Borborema, com 596 estabelecimentos (44,7% dos estabelecimentos da agricultura familiar do município); Pedras de Fogo, no Vale do Paraíba, com 577 estabelecimentos (38,6% dos estabelecimentos da agricultura familiar do

município); e Sapé, na Mata Sul, com 523 estabelecimentos (39,4% dos estabelecimentos da agricultura familiar do município).

4. Floricultura

A Floricultura estava presente em 51 estabelecimentos da agricultura familiar na Paraíba (0,04% dos 125.489 estabelecimentos da agricultura familiar do estado), com destaque novamente para o Território da Borborema, onde 22 estabelecimentos (43,1% dos estabelecimentos floricultores) produzem flores, e a Mata Sul, com 11 estabelecimentos (21,6%). (Tabela 15). O destaque municipal fica com Lagoa Seca, na Borborema, com 10 estabelecimentos da agricultura familiar produzindo flores. Essa produção é espalhada em poucas propriedades em diferentes municípios.

5. Silvicultura

A Silvicultura aparecia em 1.021 estabelecimentos, 0,8% do total de estabelecimentos da agricultura familiar do estado, com destaque para o Território da Borborema, com 368 estabelecimentos (36,0% do total) cultivando florestas através do manejo agrícola (Tabela 15). Em seguida, o Piemonte da Borborema, com 155 estabelecimentos (15,2); e o Médio Sertão, com 151 estabelecimentos (14,8% do total). O município de Taperoá, na Borborema, se destacava com 222 estabelecimentos silvicultores da agricultura familiar, 26,9% do total dos estabelecimentos da agricultura familiar do município (Tabela 15).

6. Extração vegetal

Finalmente, na extração vegetal, 18.659 estabelecimentos, 14,9% do total de estabelecimentos da agricultura familiar do estado, se dedicavam ao cultivo de produtos provenientes de espécies vegetais não plantadas (nativas) (Tabela 15). O Território da Borborema se destacava, com 5.742 estabelecimentos (30,8% do total de estabelecimentos extrativistas), seguido do Vale do Piancó, com 3.495 estabelecimentos (18,7%) e o Piemonte da Borborema, com 2.752 estabelecimentos (14,7% do total).

Entre os municípios, destacavam-se Areia, com 581 estabelecimentos (48,4% do total de estabelecimentos da agricultura familiar do município); e Alagoa Grande, com 571 estabelecimentos (51,4% do total do município), ambos na Borborema. No Vale do Piancó se destaca o município de Conceição, com 580 estabelecimentos (49,2% do total do município), e Bananeiras, no Piemonte da Borborema, com 539 estabelecimentos (32,7% do total do município).

O valor da produção vegetal nos estabelecimentos da agricultura familiar da Paraíba é maior nas lavouras temporárias, onde alcançou a cifra de R$ 244,8 milhões, 3,7 vezes o valor da produção das lavouras permanentes (Tabela 16). Os territórios da Borborema (R$ 42,4 milhões) e Mata Norte (R$ 42,1 milhões) tiveram uma participação expressiva nesse total, com 17,3% e 17,2% do valor total da produção de lavouras temporárias, respectivamente.

Tabela 15 - *Número de estabelecimentos da agropecuária familiar, por tipo de produção vegetal, por Território Rural - 2017*

Territórios	Lavouras		Horti-cultura	Flori-cultura	Silvi-cultura	Extração vegetal	Total Estab. Agropec. Familiar
	Permanentes	Temporárias					
Mata Sul	1.871	6.475	3.110	11	1	57	7.450
Brejo	1.162	4.446	503	1	66	112	5.425
Borborema	3.496	22.845	2.179	22	368	5.742	30.137
Curimataú	587	4.813	108	1	28	1.664	6.942
Cariri	83	3.430	260	5	41	508	8.173
Médio Sertão	289	5.496	221	6	151	1.607	6.680
Vale do Piancó	216	7.638	485	0	48	3.495	9.378
Médio Piranhas	19	2.207	68	0	37	339	2.809
Alto Sertão	209	7.146	220	2	4	545	8.148
Vale do Piranhas	199	3.600	142	0	12	257	4.458
Serra do Teixeira	183	5.920	151	0	79	580	6.451
Vale do Paraíba	359	8.428	1.271	1	7	764	9.200
Vale do Maringá	107	1.635	85	0	0	47	2.937
Mata Norte	1.172	5.218	1.596	1	24	190	6.283
Piemonte da Borborema	1.888	9.573	621	1	155	2.752	11.018
Total	**11.840**	**98.870**	**11.020**	**51**	**1.021**	**18.659**	**125.489**

Fonte: Censo Agropecuário/IBGE, 2017
Elaboração: DIEESE

Os municípios em destaque foram Araçagi, no Território do Brejo, com R$ 17,1 milhões; Pedras de Fogo, no Vale do Paraíba, com R$ 16,5 milhões; e Itapororoca, na Mata Norte, com R$ 13,9 milhões.

No valor da produção de lavouras permanentes, o destaque também foi o Território da Borborema, com R$ 28,5 milhões (43,6% do total), sendo que dois munícipios que compõem o território apresentaram os maiores valores da produção: Alagoa Nova, com R$ 10,9 milhões, e Areia, com R$ 9,0 milhões (Tabela 16).

No valor da Horticultura, a Mata Sul se destaca sobre o todos os demais territórios, com R$ 14,5 milhões (29,7% do total), seguida do Território da Borborema, com R$ 12,1 milhões (24,9%). Entre os munícipios, os destaques foram Lagoa Seca, na Borborema, com R$ 6,0 milhões, Conde, na Mata Sul, com R$ 5,6 milhões, e Pedra de Fogo, no Vale do Paraíba, com R$ 3,1 milhões (Tabela 16).

Na Floricultura, como são poucos produtores, o dado municipal não pode ser explicitado, para não identificar os produtores (Tabela 16).

Na Silvicultura, como também são poucos estabelecimentos em alguns territórios produtores, o valor de produção de vários estabelecimentos não pode ser revelado (Tabela 16).

No valor da extração vegetal, o destaque fica com a Borborema, com R$ 14,6 milhões (43,8% do total), com destaque para o município de Alagoa Nova, com R$ 11,2 milhões. Também se destaca o município de Cacimbas, no Médio Sertão, teve um valor de produção de R$ 3,1 milhões (Tabela 16).

Tabela 16 - *Valor da produção de origem vegetal em estabelecimentos da agricultura familiar por tipo de produção vegetal, por Território Rural (em mil reais) - 2017*

Territórios	Lavouras		Horticultura	Floricultura	Silvicultura	Extração vegetal
	Permanentes	Temporárias				
Mata Sul	14.513,00	38.729,00	14.473,00	(1)	(1)	(1)
Brejo	2.932,00	24.049,00	1.707,00	(1)	80,00	85,00
Borborema	28.514,00	42.353,00	12.116,00	(1)	158,00	14.589,00
Curimataú	1.999,00	6.104,00	14,00	(1)	(1)	4.138,00
Cariri	136,00	6.091,00	1.223,00	(1)	16,00	1.494,00
Médio Sertão	532,00	5.548,00	2.246,00	(1)	55,00	4.465,00
Vale do Piancó	378,00	11.603,00	2.995,00	(1)	98,00	4.201,00
Médio Piranhas	0,00	3.432,00	124,00	(1)	13,00	105,00
Alto Sertão	970,00	8.729,00	526,00	(1)	(1)	570,00
Vale do Piranhas	2.186,00	3.271,00	505,00	(1)	(1)	81,00
Serra do Teixeira	194,00	8.057,00	594,00	(1)	27,00	358,00
Vale do Paraíba	314,00	30.357,00	5.190,00	(1)	(1)	429,00
Vale do Maringá	426,00	1.338,00	124,00	(1)	(1)	18,00
Mata Norte	2.475,00	42.123,00	4.266,00	(1)	10,00	3,00
Piemonte da Borborema	9.774,00	12.985,00	2.599,00	(1)	108,00	2.762,00
Total	**65.343,00**	**244.769,00**	**48.702,00**	**(1)**	**559,00**	**33.297,00**

Fonte: Censo Agropecuário/IBGE, 2017
Elaboração: DIEESE
(1) Como os dados foram desagregados por municípios, em alguns o valor é inibido para não identificar o informante. EX: Determinado município só possui uma propriedade produtora de algodão, logo o valor de sua produção (ou algum outro dado) deve ser inibido. Assim, alguns subtotais podem não bater na soma ou não constar no resultado.

PRODUTOS COMERCIALIZADOS PELA AGROINDÚSTRIA FAMILIAR NA PARAÍBA, EM 2017

Entre os produtos mais comercializados pela agroindústria familiar na Paraíba, em 2017, destacaram-se o "queijo e requeijão", que representaram 61,5% (R$ 47,5 milhões) do valor total das vendas, de R$ 77,4 milhões (Tabela 17).

Em seguida apareceu o produto "carne de outros animais (verde)", com um valor de vendas de R$ 7,5 milhões (9,7% do total comercializado); seguido, pela "carne de bovinos (verde)", com R$ 6,6 milhões (8,5% das vendas); a "carne de suínos (verde), com vendas de R$ 4,3 milhões (5,6%); a "farinha de mandioca", com vendas de R$ 3,6 milhões (4,7% do total); e "doces e geleias", com vendas de R$ 2,4 milhões (3,1% do total das vendas).

Esses seis produtos responderam por 93,1% de todas as vendas de produtos da agroindústria familiar no estado da Paraíba, em 2017, somando um valor de R$ 72 milhões.

Outros 15 produtos registaram participação relativa inferior a 2% do total das vendas da agroindústria familiar nesse período. Somados, representavam um valor de R$ 5,4 milhões.

Tabela 17 - *Valor da venda de produtos da agroindústria familiar na Paraíba (em mil reais) - 2017 –*

Produtos	Valor (R$)	(%)	Produtos	Valor (R$)	(%)
Queijo e requeijão	47.542	60,6%	Pães, bolos e biscoitos	251	0,3%
Carne de outros animais(verde)	7.531	9,6%	Melado	135	0,2%
Carne de bovinos(verde)	6.601	8,4%	Aguardente de cana	82	0,1%
Carne de suínos(verde)	4.297	5,5%	Couros e peles	54	0,1%
Farinha de mandioca	3.630	4,6%	Produtos de madeira	50	0,1%
Doces e geléias	2.400	3,1%	Sucos de frutas	49	0,1%
Outros produtos	1.377	1,8%	Vinho de uva	10	0,0%
Carvão vegetal	1.176	1,5%	Arroz em grão	3	0,0%
Rapadura	744	0,9%	Licores	3	0,0%
Polpa de frutas	568	0,7%	Fubá de Milho	1	0,0%
Manteiga	475	0,6%	Total	78.468	100,0%
Goma ou tapioca	377	0,5%			

Fonte: Censo Agropecuário 2017-IBGE
Elaboração: DIEESE

VALOR DAS DESPESAS DOS ESTABELECIMENTOS DA AGRICULTURA FAMILIAR PARAIBANA, EM 2017

Na Tabela 18, foram levantadas as principais despesas efetivadas pelos agropecuaristas familiares na realização de suas tarefas produtivas.

Os principais gastos dos estabelecimentos da agricultura familiar foram com a "Compra de animais", R$ 129,2 milhões (28,9% das despesas totais);" Salários pagos", R$ 91,3 milhões (20,4%); e "Combustíveis e lubrificantes", R$ 91,1 milhões (20,3%);" Energia elétrica", R$ 78,2 milhões (17,5%);" Adubos e corretivos", R$ 50,5 milhões (11,3%); e" Agrotóxicos", R$ 7,4 milhões (1,7%). A despesa total somou R$ 447,7 milhões (Tabela 18).

Na Tabela 12 (p. 16), ficou demonstrado que o maior valor da produção da agricultura familiar na Paraíba provém da produção animal (R$ 649,7 milhões, ou 60,5% do valor total). Talvez, por isso, a maior despesa desses estabelecimentos agropecuários seja a compra de animais.

É interessante observar que a segunda maior despesa dos estabelecimentos da agricultura familiar da Paraíba, em 2017, era com "Salários pagos", praticamente no mesmo valor das despesas com "Combustíveis e lubrificantes" (Tabela 18). Outra despesa significativa nos estabelecimentos da agricultura familiar era com a "Energia elétrica". Juntas, essas quatro grandes despesas somavam R$ 389,8 milhões (87,1% do total). Por fim, apareciam as despesas com "Adubos e corretivos" (11,3% da despesa total) e com a compra de agrotóxicos, esta última com participação de apenas 1,7% no total das despesas.

A despesa com "Agrotóxicos" (R$ 7,4 milhões) adquiria importância mais destacada na Mata Sul, com R$ 1,5 milhão (20,1% da despesa total com esse item), talvez pela alta concentração da produção da horticultura nesse território. Na sequência, figuravam o Território da Mata Norte, com R$ 974 milhões gastos com "Agrotóxicos" (13,2%); e o Vale do Paraíba, com R$ 918 milhões (12,4%). Somente esses três Territórios responderam por quase a metade (45,7%) do valor gasto com agrotóxicos pelos estabelecimentos da agricultura familiar paraibana, em 2017. Esses valores devem ser relacionados com os dados que serão apresentados na Tabela 19, mais adiante.

Tabela 18 – *Valor das despesas realizadas pelos estabelecimentos da agricultura familiar por tipo de despesa (em mil reais), por Território Rural - 2017*

Territórios	Tipo de despesa					
	Compra de animais	Salários pagos	Combustíveis e lubrificantes	Energia elétrica	Adubos e corretivos	Agrotóxicos
Mata Sul	3.807,00	15.511,00	7.082,00	7.595,00	10.574,00	1.489,00
Brejo	8.308,00	4.333,00	4.493,00	3.198,00	2.931,00	774,00
Borborema	30.831,00	21.556,00	22.806,00	16.782,00	13.965,00	743,00
Curimataú	6.181,00	2.375,00	5.128,00	2.864,00	1.274,00	301,00
Cariri	11.207,00	5.782,00	9.589,00	5.378,00	1.406,00	141,00
Médio Sertão	7.228,00	4.107,00	6.204,00	4.136,00	1.383,00	233,00
Vale do Piancó	9.973,00	5.858,00	6.358,00	5.858,00	430,00	352,00
Médio Piranhas	3.916,00	2.942,00	2.520,00	2.412,00	2.255,00	127,00
Alto Sertão8	9.315,00	5.251,00	3.754,00	6.122,00	510,00	494,00
Vale do Piranhas	4.270,00	3.046,00	2.624,00	3.646,00	382,00	241,00
Serra do Teixeira	7.077,00	2.592,00	2.285,00	3.112,00	3.994,00	226,00
Vale do Paraíba	6.954,00	4.582,00	3.156,00	4.974,00	2.294,00	918,00
Vale do Maringá	3.483,00	3.156,00	3.446,00	2.629,00	728,00	101,00
Mata Norte	3.804,00	3.953,00	5.165,00	4.634,00	4.128,00	974,00
Piemonte da Borborema	12.813,00	6.287,00	6.459,00	4.867,00	4.249,00	284,00
Total	129.167,00	**91.331,00**	**91.069,00**	**78.207,00**	**50.503,00**	**7.398,00**

Fonte: Censo Agropecuário/IBGE, 2017
Elaboração: DIEESE
.

UTILIZAÇÃO DE AGROTÓXICOS PELOS ESTABELECIMENTOS DA AGROPECUÁRIA PARAIBANA, EM 2017

Pelas informações do Censo Agropecuário de 2017, a utilização de agrotóxicos era relativamente semelhante, quando se compara a porcentagem de estabelecimentos da agricultura familiar e a porcentagem de estabelecimentos não familiares que usavam esses produtos, embora a Tabela 19 não trate da quantidade utilizada em cada grupo. Pelos dados apresentados anteriormente, na Tabela 18, conclui-se que muitos estabelecimentos da agricultura familiar utilizavam agrotóxicos, porém em quantidades pequenas, já que a despesa com esses produtos era módica.

Pelos dados da Tabela 19, a seguir, observa-se que, entre os estabelecimentos da agropecuária familiar, a média da utilização de agrotóxicos foi de 33,2%, sendo que 66,6% dos estabelecimentos não os utilizaram. A maior utilização se deu no Vale do Piranhas, em 61,1% dos estabelecimentos, e no Médio Piranhas, em 60,7%. A menor utilização ocorreu no Cariri, em 9,4%.

Entre os estabelecimentos da agropecuária não familiar, 28,2% usaram agrotóxicos e 71,6% não utilizaram. As maiores taxas de utilização se deram, também, no Vale do Piranhas, com 57,6%, e Médio Piranhas, com 55,7%. A menor taxa de utilização ocorreu no Cariri, com 7,6%.

Tabela 19 – *Participação dos estabelecimentos da agropecuária paraibana por tipos, segundo uso de agrotóxico, por Território Rura - 2017*

Territórios	Agropecuária familiar			Agropecuária não familiar		
	Utilizou (%)	Não utilizou (%)	Total de estabelecimentos	Utilizou(%)	Não utilizou(%)	Total de estabelecimentos
Mata Sul	38,3%	61,7%	7.450	32,2%	67,7%	2.465
Brejo	28,1%	71,6%	5.425	26,9%	72,8%	1.906
Borborema	16,7%	83,3%	30.137	15,4%	84,6%	11.561
Curimataú	49,3%	50,7%	6.942	35,3%	64,6%	2.163
Cariri	9,4%	90,6%	8.173	7,6%	92,2%	2.785
Médio Sertão	44,7%	55,3%	6.680	44,0%	56,0%	1.933
Vale do Piancó	34,6%	65,4%	9.378	33,4%	66,6%	2.473
Médio Piranhas	60,7%	39,1%	2.809	55,7%	43,9%	756
Alto Sertão	54,3%	45,6%	8.148	51,3%	45,5%	1.835
Vale do Piranhas	61,1%	38,7%	4.458	57,6%	42,0%	979
Serra do Teixeira	31,8%	68,1%	6.451	30,0%	70,0%	1.182
Vale do Paraíba	49,8%	50,0%	9.200	41,4%	58,3%	2.557
Vale do Maringá	47,4%	52,4%	2.937	44,9%	55,0%	1.019
Mata Norte	21,4%	75,7%	6.283	23,0%	74,5%	1.920
Piemonte da Borborema	32,3%	67,6%	11.018	29,3%	70,4%	2.195
Total	**33,2%**	**66,6%**	**125.489**	**28,2%**	**71,6%**	**37.729**

Fonte: Censo Agropecuário/IBGE, 2017
Elaboração: DIEESE

Alguns municípios destacavam-se pela baixa utilização de agrotóxicos, tanto entre os estabelecimentos da agropecuária familiar, quanto da agropecuária não familiar.

Entre os municípios do Território da Borborema, destacavam-se Alcantil, onde 99,7% dos estabelecimentos da agricultura familiar e 100% dos estabelecimentos da agropecuária não familiar não utilizavam agrotóxicos; Matinhas (99,9% dos familiares e 99,6% dos não familiares); Soledade (99,7% e 99,6%, respectivamente); e Algodão de Jandira (99,5% e 98,8%).

No Território do Vale do Piancó, o município de Coremas também se destacava, com 99,3% dos estabelecimentos familiares e 100% dos não familiares sem utilização de agrotóxicos.

No Território do Cariri, em 13 dos seus 18 municípios, mais de 90% dos estabelecimentos da agricultura familiar e não familiares não utilizavam agrotóxicos.

OBTENÇÃO DE ORIENTAÇÃO TÉCNICA PELOS ESTABELECIMENTOS DA AGRICULTURA FAMILIAR PARAIBANA, EM 2017

Declararam receber algum tipo de orientação técnica somente 21.123 (16,8%) dos 125.489 estabelecimentos da agricultura familiar da Paraíba, em 2017 (Tabela 20). Os territórios com maior porcentagem de estabelecimentos que receberam orientação técnica foram o Alto Sertão (44,3%); o Vale do Maringá (39,3%); e o Vale do Piranhas (35,1% dos estabelecimentos).

Mais de 83% dos estabelecimentos da agricultura familiar paraibana não receberam qualquer orientação técnica, em 2017. Esse percentual superava os 80% em 11 dos 15 Territórios. A maior porcentagem desses estabelecimentos estava no Território da Mata Sul (91,7%)

Em relação à oferta de orientação técnica, destacava-se o papel relevante dos governos (federal, estadual ou municipais). Na Paraíba, 13,5% dos estabelecimentos da agricultura familiar receberam alguma orientação técnica por parte desses órgãos, com destaque para o Vale do Maringá, onde somavam 38,1% (Tabela 20).

Entre os municípios, destacavam-se Santa Terezinha, no Médio Sertão, onde 66,5% dos estabelecimentos receberam orientação técnica do governo; Baia da Traição, na Mata Norte, com 65,1%; Lagoa, no Vale do Maringá, com 64,3%; e São José dos Ramos, no Vale do Paraíba, com 61,6%.

Outras fontes de orientação técnica tiveram importância mais modesta. A orientação do próprio produtor foi informada por 2,3% dos estabelecimentos da agropecuária familiar, com destaque para o Território do Alto Sertão, com 13,5% dos estabelecimentos; a orientação por parte das cooperativas foi informada somente por 0,8% deles; e das Empresas/ONGs ou Sistema "S" por apenas 0,5%. Importante destacar que os recursos dessas entidades ou instituições podem também ser recursos públicos, oriundos de convênios ou projetos (Tabela 20).

Entre os munícipios, a orientação técnica do próprio produtor foi informada por 32,1% dos estabelecimentos em São Bento; 30%, em Brejo da Cruz; 29,7%, em Mato Grosso; e 27,6%, em Belém do Brejo da Cruz, todos no Território do Alto Sertão. A orientação técnica feita por cooperativas destacava-se em Santana do Garrote, no Vale do Piancó, com 15,2% dos estabelecimentos da agropecuária familiar; Princesa Izabel, com 11,1%, na Serra do Teixeira; Alagoa Grande, com 8,9%, na Borborema; e Nova Floresta, com 6,8%, no Curimataú.

O papel das empresas/ONGs/Sistema "S" era muito pouco representativo, com apenas algum destaque para os estabelecimentos da agricultura familiar dos municípios de Areial, com 8,5%, e Montadas, com 5,9%, ambos no Território da Borborema; e Cacimbas, com 5,9%, no Médio Sertão.

Ainda no âmbito dos municípios, Capim destacou-se negativamente, com 100% dos estabelecimentos sem obter qualquer orientação técnica, e Cuité do Mamanguape, com 99,3%, ambos no Território da Mata Norte. Também Nova Olinda, com 99,4%, no Vale do Piancó, e Serra Redonda, com 98,9%, no Vale do Paraíba, figuravam entre os municípios cujos estabelecimentos praticamente não foram contemplados pela orientação técnica.

Tabela 20 - *Participação dos estabelecimentos da agricultura familiar paraibana, que receberam ou não orientação técnica*, por Território Rural* - 2017

	Estabelecimentos que receberam orientação técnica						Estabelecimentos que não receberam orientação técnica
Territórios	**Total**	**Do governo (federal, estadual ou municipal)**	**Própria ou do próprio produtor**	**De cooperativas**	**De empresa / ONG / Sistema S**	**De outra origem**	
Mata Sul	8,3%	6,4%	0,8%	0,7%	0,1%	0,7%	91,7%
Brejo	11,4%	9,9%	0,8%	0,2%	0,2%	0,4%	88,6%
Borborema	15,2%	11,4%	2,1%	1,2%	1,0%	0,6%	84,8%
Curimataú	14,8%	8,7%	4,7%	0,6%	0,7%	2,4%	85,2%
Cariri	19,1%	15,6%	2,2%	0,7%	0,2%	1,1%	80,9%
Médio Sertão	25,3%	18,7%	5,0%	0,4%	1,6%	0,8%	74,7%
Vale do Piancó	13,1%	8,3%	4,0%	1,2%	0,1%	0,1%	86,9%
Alto Sertão	44,3%	34,2%	13,5%	0,2%	0,0%	0,0%	55,7%
Alto Sertão	12,9%	10,8%	1,4%	0,2%	0,5%	0,3%	87,1%
Vale do Piranhas	35,1%	31,8%	2,8%	0,1%	0,5%	1,0%	64,9%
Serra do Teixeira	12,9%	11,0%	1,5%	1,8%	0,1%	0,2%	87,1%
Vale do Paraíba	18,3%	16,7%	0,5%	0,8%	0,3%	0,6%	81,7%
Vale do Maringá	39,3%	38,1%	2,3%	0,1%	0,3%	0,1%	60,7%
Mata Norte	11,2%	9,7%	1,0%	0,6%	0,2%	0,3%	88,8%
Piemonte da Borborema	14,2%	12,5%	0,5%	0,5%	0,7%	0,6%	85,8%
Total	**16,8%**	**13,5%**	**2,3%**	**0,8%**	**0,5%**	**0,6%**	**83,2%**

Fonte: Censo Agropecuário/IBGE, 2017
Elaboração: DIEESE
* A soma das atividades impossibilita a totalização dos estabelecimentos por município.

ATRIBUTOS PESSOAIS DOS/AS RESPONSÁVEIS PELOS ESTABELECIMENTOS DA AGRICULTURA FAMILIAR NA PARAÍBA

Esta seção apresenta o perfil dos/as responsáveis pelos estabelecimentos da agricultura familiar da Paraíba em 2017, conforme os atributos pessoais: sexo; cor da pele; idade; escolaridade e relação com a terra.

DISTRIBUIÇÃO DOS RESPONSÁVEIS PELOS ESTABELECIMENTOS DA AGRICULTURA FAMILIAR DA PARAÍBA, POR SEXO

A agricultura familiar na Paraíba é uma atividade econômica exercida predominantemente por trabalhadores do sexo masculino. Os produtores considerados responsáveis pelas unidades de produção agricultura familiar eram, majoritariamente, homens, concentrando 76% do total. As mulheres representavam apenas 24% (Tabela 21).

A maior participação das mulheres responsáveis pelos estabelecimentos da agricultura familiar se dá nos territórios da Mata Norte (32,3%) e Borborema (31,2%). As menores nos Território do Vale do Piancó (12,4%) e Médio Piranhas (14,0%).

Tabela 21 - *Número de estabelecimentos da agricultura familiar paraibana, segundo o sexo do(a) responsável, por Território Rural - 2017*

Territórios	Responsáveis Homens	Responsáveis Mulheres	Total	% Mulheres
Mata Sul	5.531	1.919	7.450	25,8%
Brejo	4.153	1.272	5.425	23,4%
Borborema	20.745	9.392	30.137	31,2%
Curimatau	5.215	1.727	6.942	24,9%
Cariri	6.108	2.065	8.173	25,3%
Médio Sertão	4.952	1.728	6.680	25,9%
Vale do Piancó	8.213	1.165	9.378	12,4%
Médio Piranhas	2.415	394	2.809	14,0%
Alto Sertão	6.979	1.169	8.148	14,3%
Vale do Piranhas	3.771	687	4.458	15,4%
Serra do Teixeira	5.353	1.098	6.451	17,0%
Vale do Paraíba	6.680	2.520	9.200	27,4%
Vale do Maringá	2.460	477	2.937	16,2%
Mata Norte	4.253	2.030	6.283	32,3%
Piemonte da Borborema	8.535	2.483	11.018	22,5%
Total	**95.363**	**30.126**	**125.489**	**24,0%**

Fonte: Censo Agropecuário/IBGE, 2017
Elaboração: DIEESE

DISTRIBUIÇÃO DOS RESPONSÁVEIS PELOS ESTABELECIMENTOS DA AGRICULTURA FAMILIAR DA PARAÍBA, POR COR DA PELE

O Censo Agropecuário de 2017, pela primeira vez, investigou a cor da pele dos/as produtores/as responsáveis pelos estabelecimentos da agricultura familiar. Sob esse aspecto, mais da metade dos/as responsáveis se declarou de cor parda (56% do total), com destaque para os Territórios do Piemonte da Borborema e Serra do Teixeira, onde 64,1% e 62,0%, respectivamente, se declararam desta cor (Tabela 22).

O percentual de estabelecimentos cujos responsáveis se declararam da cor branca foi de 34,6%, com destaque para o Território do Médio Piranhas, onde os brancos representavam 47,2% dos responsáveis. Em terceiro lugar, em 7,7% dos estabelecimentos, os responsáveis se declararam pretos, com destaque para o Território da Mata Sul (13,5%). O contingente que se declarou indígena não chegou a 1%, com destaque para o Território da Mata Norte, com 14,3%. Os que se declararam amarelos eram 0,4%, com destaque para o Médio Sertão, com 2,2% dos responsáveis pelos estabelecimentos da agropecuária familiar.

Tabela 22 – *Participação dos estabelecimentos da agricultura familiar paraibana, segundo a cor da pele do(a) responsável, por Território Rural* - 2017

Territórios	Branca	Parda	Preta	Amarela	Indígena
Mata Sul	29,5%	56,6%	13,5%	0,2%	0,1%
Brejo	32,7%	58,0%	9,3%	0,0%	0,0%
Borborema	35,1%	55,5%	7,5%	0,3%	0,1%
Curimataú	31,3%	59,6%	7,5%	1,6%	0,1%
Cariri	40,9%	51,9%	6,6%	0,4%	0,0%
Médio Sertão	32,8%	56,1%	8,4%	2,2%	0,5%
Vale do Piancó	37,1%	55,0%	7,0%	0,3%	0,7%
Médio Piranhas	47,2%	49,1%	3,7%	0,0%	0,0%
Alto Sertão	42,9%	49,3%	7,6%	0,2%	0,0%
Vale do Piranhas	44,5%	50,3%	5,1%	0,1%	0,0%
Serra do Teixeira	30,4%	62,0%	6,5%	0,0%	0,0%
Vale do Paraíba	30,5%	58,9%	10,2%	0,3%	0,1%
Vale do Maringá	39,0%	55,0%	5,8%	0,0%	0,2%
Mata Norte	28,0%	50,1%	7,6%	0,0%	14,3%
Piemonte da Borborema	29,3%	64,1%	6,2%	0,4%	0,1%
Total	**34,6%**	**56,0%**	**7,7%**	**0,4%**	**0,9%**

Fonte: Censo Agropecuário/IBGE, 2017
Elaboração: DIEESE

DISTRIBUIÇÃO DOS RESPONSÁVEIS PELOS ESTABELECIMENTOS DA AGRICULTURA FAMILIAR DA PARAÍBA, POR FAIXA ETÁRIA

Nos dados da Tabela 23, a seguir, observa-se que 22,7% dos estabelecimentos da agropecuária paraibana (cerca de 28 mil) eram dirigidos por responsáveis com idade entre 55 e 65 anos. Outros 30,3% (cerca de 38 mil) eram dirigidos por produtores com idade acima de 65 anos. Ou seja, mais da metade (53%) dos estabelecimentos da agricultura familiar na Paraíba eram dirigidos por produtores com 55 anos ou mais, já na idade da aposentadoria como segurado especial pelo Instituto Nacional do Seguro Social (INSS).

Em vários municípios, constata-se uma grande presença de estabelecimentos da agricultura familiar (entre 45% e 49,4%), cujos responsáveis tinham idade superior a 65 anos. Destacam-se os casos de Quixaba (49,4%), no Médio Sertão; Congo (48,9%), no Cariri; Lastro (47,5%), no Vale do Piranhas; São Domingos (45,6%), no Vale do Maringá; Barra de São Miguel (45,3%), na Borborema; e Caldas Brandão (45%), no Vale do Paraíba.

Esses números evidenciam um problema da agricultura familiar na Paraíba - na verdade em todo o Brasil -, que é o envelhecimento dos produtores familiares rurais, a baixa renovação por produtores mais novos e as dificuldades na sucessão da propriedade, tornando o envelhecimento um agravante social entre esses produtores.

Tabela 23 – *Participação dos estabelecimentos da agricultura familiar paraibana, segundo a faixa etária do responsável - 2017*

Territórios	Menor de 25 anos	De 25 a menos de 35 anos	De 35 a menos de 45 anos	De 45 a menos de 55 anos	De 55 a menos de 65 anos	De 65 anos e mais
Mata Sul	2,0%	9,7%	18,1%	24,1%	21,6%	24,4%
Brejo	1,6%	6,9%	14,9%	21,3%	22,6%	32,7%
Borborema	1,4%	7,6%	14,6%	20,7%	23,1%	32,5%
Curimataú	1,9%	9,5%	16,7%	20,2%	21,7%	29,9%
Cariri	1,5%	6,8%	14,1%	20,8%	23,2%	33,5%
Médio Sertão	1,9%	8,3%	15,2%	21,4%	23,4%	29,8%
Vale do Piancó	2,0%	9,9%	17,5%	20,9%	23,1%	26,6%
Médio Piranhas	0,6%	5,7%	13,3%	22,3%	26,9%	31,2%
Alto Sertão	1,1%	7,5%	16,3%	20,8%	22,4%	32,0%
Vale do Piranhas	1,4%	7,9%	15,9%	20,9%	23,4%	30,6%
Serra do Teixeira	1,8%	9,3%	18,1%	21,7%	20,8%	28,3%
Vale do Paraíba	1,7%	8,8%	16,4%	22,6%	22,7%	27,9%
Vale do Maringá	0,7%	5,6%	12,5%	21,1%	25,2%	34,9%
Mata Norte	2,9%	9,7%	16,2%	21,3%	20,2%	29,8%
Piemonte da Borborema	1,8%	8,2%	16,5%	22,4%	22,0%	29,1%
Total	**1,6%**	**8,2%**	**15,8%**	**21,4%**	**22,7%**	**30,3%**

Fonte: Censo Agropecuário/IBGE, 2017
Elaboração: DIEESE

DISTRIBUIÇÃO DOS RESPONSÁVEIS PELOS ESTABELECIMENTOS DA AGRICULTURA FAMILIAR DA PARAÍBA, POR NÍVEL DE ESCOLARIDADE

O nível de escolaridade dos responsáveis pelos estabelecimentos da agricultura familiar da Paraíba demonstra que quase ¼ (24,2%) deles nunca frequentou a escola, com destaque para os Territórios do Vale do Piancó (35,8%) e da Mata Norte, com 34,3% (Tabela 24). No município de Olho D´Água, no Vale do Piancó, 63,4% dos responsáveis não eram alfabetizados. Em São Domingos, no Vale do Maringá, 57,4% dos responsáveis pelos estabelecimentos da agricultura familiar nunca frequentaram a escola.

Outros 47,5% dos responsáveis pelos estabelecimentos da agricultura familiar na Paraíba tinham cursado apenas até a quinta série do Ensino Fundamental ou equivalente, com destaque para o Alto Sertão, com 57,7%. Em seguida, 19,4% dos responsáveis tinham o Ensino Fundamental completo ou equivalente; 7,5% tinham o Ensino Médio ou equivalente; e apenas 1,3% tinham o Ensino Superior, Mestrado ou Doutorado.

Vale a pena destacar alguns dados municipais no que diz respeito à escolaridade dos responsáveis pelos estabelecimentos da agropecuária familiar: Sertãozinho, no Brejo, tinha apenas 6,2% de responsáveis que nunca frequentaram a escola e 44,4% até o primeiro grau. Curral Velho, no Vale do Piancó, tinha 11,3% dos responsáveis que nunca frequentaram escola e 73,7% que frequentaram até o Ensino Fundamental I. São Bentinho, no Vale do Maringá, tinha 16,4% que nunca frequentaram a escola e 74,4% dos responsáveis que frequentaram até o Ensino Fundamental I.

Em Bayeux, na Mata Sul, com declaração de apenas 18 agropecuaristas familiares responsáveis, quatro tinham nível superior.

Tabela 24 – *Participação dos estabelecimentos da agricultura familiar paraibana, segundo a escolaridade do responsável, por Território Rural - 2017*

Territórios	Nunca frequentou escola	Até o Fundamental (*)	Até o Fundamental II (**)	Até o Ensino Médio (***)	Ensino Superior (****)	Total de Estab.
Mata Sul	26,9%	37,4%	23,4%	10,4%	1,9%	7.450
Brejo	20,6%	50,0%	18,8%	8,5%	2,1%	**5.425**
Borborema	19,1%	53,1%	19,8%	6,7%	1,2%	**30.137**
Curimataú	20,6%	45,7%	25,4%	7,4%	0,8%	**6.942**
Cariri	18,6%	51,2%	19,5%	9,2%	1,6%	**8.173**
Médio Sertão	22,3%	46,3%	21,2%	8,5%	1,6%	**6.680**
Vale do Piancó	35,8%	41,1%	13,9%	8,0%	1,2%	**9.378**
Médio Piranhas	29,5%	33,4%	27,6%	8,0%	1,5%	**2.809**
Alto Sertão	19,9%	57,7%	14,6%	6,5%	1,4%	**8.148**
Vale do Piranhas	30,2%	44,3%	16,4%	8,0%	1,1%	**4.458**
Serra do Teixeira	27,0%	49,1%	17,8%	5,7%	0,4%	**6.451**

continua

Territórios	Nunca frequentou escola	Até o Fundamental (*)	Até o Fundamental II (**)	Até o Ensino Médio (***)	Ensino Superior (****)	Total de Estab.
Vale do Paraíba	25,0%	46,3%	19,4%	8,1%	1,3%	**9.200**
Vale do Maringá	25,2%	51,9%	15,3%	6,4%	1,2%	**2.937**
Mata Norte	34,3%	34,5%	20,9%	8,9%	1,4%	**6.283**
Piemonte da Borborema	27,1%	45,9%	20,1%	5,9%	1,0%	**11.018**
Total	**24,2%**	**47,5%**	**19,4%**	**7,5%**	**1,3%**	**125.489**

Fonte: Censo Agropecuário/IBGE, 2017
(*) Inclui Classe de alfabetização - CA; Alfabetização de Jovens e Adultos - AJA; antigo primário (elementar)
(**) Antigo ginasial; Regular do Ensino Fundamental; Educação de Jovens e Adultos (EJA) e Supletivo do Ensino Fundamental
(***) Antigo Científico/Clássico etc.; Regular do Ensino Médio; Técnico de ensino médio; EJA - educação de jovens e adultos e supletivo do Ensino Médio
(****) Graduação/mestrado/doutorado
Elaboração: DIEESE

DISTRIBUIÇÃO DOS RESPONSÁVEIS PELOS ESTABELECIMENTOS DA AGRICULTURA FAMILIAR PARAIBANA, EM RELAÇÃO À POSSE DA TERRA

A condição do responsável pelo estabelecimento agropecuário familiar em relação à posse da terra[5] era, principalmente, a de proprietário, em 72,6% do total dos 125.489 estabelecimentos. (Tabela 25). Destaque para os territórios da Serra do Teixeira, com 84,7%, e do Cariri, com 83,3%. Entre os municípios, destacavam-se Igaracy, no Vale do Piancó, onde 100% dos 467 responsáveis pelos estabelecimentos da agricultura familiar eram proprietários. Em Cuité de Mamanguape, 98,6% dos responsáveis pelos 577 estabelecimentos eram proprietários; e em Lagoa de Dentro, 98,7% dos 559 responsáveis pelos estabelecimentos detinham a propriedade das terras.

Com acesso mais precário a terras estavam os outros 34.360 responsáveis pelos estabelecimentos da agricultura familiar, ou 27,4% do total (Tabela 25). Os Concessionários(as) ou Assentados(as) aguardando titulação definitiva[6] (7,6% do total) destacavam-se no Território da Mata Sul, com 25,2%, e Vale do Paraíba, com 13,7%. Na Mata Sul, o município de Sapé tinha 51,1% dos 1.328 responsáveis pelos estabelecimentos da agricultura familiar nessa condição; Caaporã tinha 48,3% dos responsáveis pelos seus 396 estabelecimentos e Cruz do Espirito Santo tinha 39,2% dos 1.325 responsáveis pelos estabelecimentos. Na Mata Norte, também se destacavam os municípios de Marizópolis, com 69% dos 158 responsáveis pelos estabelecimentos, e Baía da Traição, com 59% dos 441 responsáveis. E o município de São Miguel

5. A condição do proprietário foi acatada independentemente da dimensão ou da proporção das terras do estabelecimento que se enquadrasse na situação terras próprias. Não havendo terras próprias, a condição do produtor seria aquela que, obedecida a ordem das categorias, correspondesse à maior porcentagem da área das terras do estabelecimento. https://biblioteca.ibge.gov.br/visualizacao/periodicos/3096/agro_2017_resultados_definitivos.pdf
6. Produtor com área de terras concedidas por órgão fundiário, sem título definitivo (inclusive assentamento e com concessão de direito real de uso) até a data de referência.

do Taipu, no Vale do Paraíba, com 57,3% dos 606 responsáveis pelos estabelecimentos. No total, eram 29 municípios com mais de 20% dos responsáveis pelos seus estabelecimentos nessa condição.

A presença de arrendatários[7] entre os responsáveis pelos estabelecimentos da agricultura familiar era pequena (1,6%), com exceção do município de Bayeux, onde 66,7% dos responsáveis pelos 18 estabelecimentos estavam nessa condição. Entre os parceiros[8], a presença de estabelecimentos da agricultura familiar também é pequena (3,1% dos responsáveis), sendo que somente no Território do Médio Piranhas o percentual é mais elevado, chegando a 12,1% (Tabela 25).

Tabela 25 – *Participação dos estabelecimentos da agricultura familiar paraibana, segundo a condição do(a) responsável, em relação à posse da terra - 2017*

Territórios	Proprietário(a)	Concessionário (a) ou assentado (a) aguardando titulação definitiva	Arrendatário(a)	Parceiro(a)	Comodatário(a)	Ocupante	Produtor sem área	Total
Mata Sul	58,5%	25,2%	2,5%	0,8%	10,5%	2,4%	0,1%	7.450
Brejo	76,0%	6,3%	2,1%	1,9%	11,1%	1,7%	0,8%	5.425
Borborema	75,7%	4,3%	0,8%	2,4%	14,5%	2,2%	0,1%	30.137
Curimataú	70,6%	10,7%	0,3%	4,2%	11,7%	2,4%	0,1%	6.942
Cariri	83,3%	6,2%	0,3%	1,4%	4,4%	4,1%	0,2%	8.173
Médio Sertão	71,9%	6,1%	2,6%	3,2%	13,4%	2,3%	0,6%	6.680
Vale do Piancó	73,6%	1,6%	4,3%	5,9%	12,3%	1,3%	1,1%	9.378
Médio Piranhas	74,4%	1,2%	1,5%	12,1%	7,8%	2,7%	0,4%	2.809
Alto Sertão	75,1%	4,0%	1,1%	2,1%	11,5%	2,7%	3,5%	8.148
Vale do Piranhas	61,6%	12,5%	1,3%	3,4%	16,1%	2,8%	2,4%	4.458
Serra do Teixeira	84,7%	0,1%	1,0%	3,3%	10,4%	0,2%	0,4%	6.451
Vale do Paraíba	58,0%	13,7%	3,7%	3,4%	18,3%	2,4%	0,4%	9.200
Vale do Maringá	70,3%	7,3%	1,3%	4,3%	15,5%	1,1%	0,3%	2.937
Mata Norte	74,6%	11,6%	2,1%	1,3%	5,8%	1,7%	2,9%	6.283
Piemonte da Borborema	71,9%	9,8%	1,0%	3,7%	9,8%	2,5%	1,2%	11.018
Total	**72,6%**	**7,6%**	**1,6%**	**3,1%**	**12,0%**	**2,2%**	**0,8%**	**125.489**

Fonte: Censo Agropecuário/IBGE, 2017
Elaboração: DIEESE

Os Comodatários[9] eram responsáveis por 12% dos estabelecimentos da agricultura familiar paraibana. As maiores participações verificavam-se nos Territórios do Vale do Paraíba, com 18,3%, e Vale do Piranhas, com 16,1%. No Município de Santa Rita, 48,1% de seus 320 estabelecimentos eram de comodatá-

7. Produtor que explora terras de terceiros, mediante pagamento de uma quantia fixa, previamente ajustada, em dinheiro ou sua equivalência em produtos.
8. Produtor que explora terras de terceiros, mediante pagamento de parte da produção (meia, terça, quarta etc.), previamente acordado entre as partes.
9. Produtor que explora terras de terceiros gratuitamente mediante contrato ou acerto entre as partes, no qual somente o comodatário assume as obrigações.

rios. Nos municípios de Gabo Bravo, Borborema, e Salgadinho, os comodatários estavam presentes em 44,4% dos estabelecimentos da agricultura familiar (Tabela 17).

É baixa a presença de Ocupantes[10](produtores que exploram terras pertencentes a terceiros, públicas ou privadas), com apenas 2,21% dos responsáveis pelos estabelecimentos de agricultura familiar em todo o estado, com destaque para o Cariri, com 4,12% (Tabela 17). O município de Mataracá, na Mata Norte, tinha 27,5% dos responsáveis pelos seus 51 estabelecimentos de agricultura familiar nessa condição; e Gurjão, no Cariri, tinha 24,1% dos 158 responsáveis pelos estabelecimentos como ocupantes.

Os produtores sem área[11], eram apenas 0,8% dos responsáveis pelos estabelecimentos da agricultura familiar, com destaque para o Território do Alto Sertão, com 3,5% (Tabela 25). Entre os municípios, destacavam-se Bernadino Batista, no Alto Sertão, com 26,8% dos 254 responsáveis pelos estabelecimentos; e Tacimã, no Piemonte da Borborema, com 19,3% dos 576 responsáveis.

PESSOAL OCUPADO NOS ESTABELECIMENTOS DA AGRICULTURA FAMILIAR NA PARAÍBA, EM 2017

Os estabelecimentos agropecuários da Paraíba ocupavam 424.056 pessoas, sendo 311.176 (73,4%) em estabelecimentos familiares e 112.880 (26,6%) em estabelecimentos não familiares (Tabela 26).

Nos estabelecimentos da agropecuária familiar, o pessoal ocupado compunha-se, principalmente, de trabalhadores/as com laços de parentesco com o produtor responsável pelo estabelecimento [12] (274.971 pessoas), 88,4% do total ocupado nesses estabelecimentos (Tabela 26). Entre os que não possuíam laços de parentesco com esses produtores familiares responsáveis, os trabalhadores temporários aparecem em maior número, com 32.440 ocupados, 10,4% do total na agropecuária familiar. Os trabalhadores permanentes eram apenas 3.235 (1%) dos ocupados na agricultura familiar e os parceiros somavam 530 trabalhadores (0,2%).

A Borborema era o território com maior número de ocupados: 107 mil, no total, sendo 76.640 nos estabelecimentos da agropecuária familiar. Ainda em relação aos estabelecimentos da agropecuária familiar, a Borborema também aparece com o maior número de trabalhadores temporários (5.927) e permanentes (980).

10. Produtor que explora terras pertencentes a terceiros (públicas ou particulares), pela qual o produtor, na data de referência, nada pagava por seu uso (ocupação ou posse)
11. Produtor que exerce explorações agropecuárias para as quais não há a necessidade de possuir uma área circunscrita ou um espaço físico delimitado, aproveitando-se das oportunidades oferecidas pelas circunstâncias locais e pela natureza da região para exercer suas atividades produtivas (apicultor; extrativistas de matas ou florestas, a exemplo de babaçu, castanha-do-brasil, látex, lenha etc.; criador de animais em beira de estradas; produtor em vazantes de rios; em roça itinerantes; e em beira de estradas). Produtor que, no período de referência, produziu em terras arrendadas, em parceria ou ocupadas, mas que, na data de referência, não estava mais com uso dessas terras.
12. Cônjuge ou companheiro(a) do mesmo sexo ou de sexo diferente, filho(a) do produtor e do cônjuge, filho(a) somente do produtor, filho(a) somente do cônjuge, genro ou nora, pai, mãe, padrasto, madrasta, sogro(a), neto(a), bisneto(a), irmão ou irmã, avô(ó), outros parentes (tio/a, sobrinho/a, primo/a, cunhado/a, ou menor sob guarda ou tutela), e enteado(a) do produtor. Foram considerados, também, neste contexto, os agregados que, apesar de não terem laços de parentesco com o núcleo familiar, são considerados por seus membros como integrantes da família.

Entre os municípios, Monteiro, no Cariri, foi o que registrou o maior número de ocupados (8.562, no total), com 6.193 trabalhadores em estabelecimentos da agropecuária familiar, sendo 5.258 com laços familiares com o produtor responsável e 858 ocupados temporários. Campina Grande, na Borborema, vem em seguida, com 6.148 ocupados no total, sendo 3.842 na agropecuária familiar. Destes, 3.339 tinham laço de parentesco com o produtor responsável e 480 eram ocupados temporários.

Tabela 26 – *Pessoal ocupado nos estabelecimentos da agropecuária paraibana - 2017*

Territórios	Número de ocupados na agropecuária familiar					Nº de ocupados na agropecuária não familiar	Total de Ocupados na agropecuária paraibana
	Total	Com laço de parentesco com o produtor	Sem laço de parentesco com o produtor				
			Permanentes	Temporários	Parceiros		
Mata Sul	20.017	17.008	265	2.724	20	11.458	31.478
Brejo	13.085	11.672	129	1.262	22	5.605	18.690
Borborema	76.640	69.559	980	5.927	174	30.367	107.009
Curimataú	18.510	16.862	104	1.509	35	5.810	24.320
Cariri	20.884	18.301	248	2.322	13	8.250	29.134
Médio Sertão	18.627	16.642	216	1.739	30	5.851	24.478
Vale do Piancó	20.661	18.066	215	2.329	51	6.110	26.786
Médio Piranhas	6.213	5.645	136	424	8	2.181	8.394
Alto Sertão	17.026	14.796	139	2.070	21	4.070	21.134
Vale do Piranhas	9.221	8.136	64	1.003	18	2.657	11.878
Serra do Teixeira	17.485	15.350	23	2.091	21	3.626	21.111
Vale do Paraíba	22.112	18.999	134	2.948	31	8.306	30.418
Vale do Maringá	6.682	5.922	208	529	23	2.741	9.425
Mata Norte	15.285	13.412	93	1.778	2	9.299	24.584
Piemonte da Borborema	28.728	24.601	281	3.785	61	6.549	35.277
Total	**311.176**	**274.971**	**3.235**	**32.440**	**530**	**112.880**	**424.056**

Fonte: Censo Agropecuário/IBGE, 2017
Elaboração: DIEESE

CONSIDERAÇÕES FINAIS

Como "Considerações finais", as informações e as análises efetuadas nas seções anteriores estão sintetizadas nos itens que se seguem.

- O estado da Paraíba tinha, em ano ,97% do seu território com predomínio do bioma da Caatinga. Sua população era de 4,1 milhões habitantes, em 223 municípios, sendo 967 mil.013 (24%) residentes em áreas rurais.
- Em 14 dos 15 territórios em que se divide o estado, o valor pago aos beneficiários da Previdência Rural, em 2020, superou a marca de 50% do valor total dos benefícios.
- Os recursos transferidos via Previdência Rural equivaliam a 93% do valor total do Fundo de Participação dos Municípios, sendo que, em 11 territórios, os valores da Previdência Rural superaram as transferências recebidas do FPM, com destaque para o Território de Serra do Teixeira, onde os recursos previdenciários rurais foram 74% superiores às transferências do FPM.
- Quando se consideram os recursos previdenciários totais (urbanos + rurais), em 14 territórios os valores previdenciários superavam o valor dos repasses do FPM, à exceção de Piemonte da Borborema, onde o valor do FPM era 57% maior.
- O Produto Interno Bruto (PIB) da Paraíba alcançou cerca de R$ 68 bilhões, em 2019, segundo o IBGE. Esse valor representava 0,9% do PIB nacional e 6,5% do PIB do Nordeste. O setor com a maior participação foi o de Serviços, com cerca de R$ 29 bilhões (42% do PIB estadual), seguido da administração, com R$ 20 bilhões (29%).
- O setor agropecuário representava apenas pouco mais de 3% do PIB estadual, alcançando R$ 2,2 bilhões. O destaque era o Território do Vale do Paraíba, com um PIB total de cerca de R$ 2 bilhões, com participação de 12% do setor agropecuário.
- Segundo o Censo Agropecuário de 2017, a região Nordeste concentrava 46% do total de estabelecimentos da agricultura familiar no Brasil, somando 1,8 milhão de unidades produtivas. Entre os estados da região Nordeste, a Paraíba participava com 6,8% dos estabelecimentos da agropecuária familiar.
- Eram 125.489 os estabelecimentos da agricultura familiar na Paraíba, representando 77% do total de 163 mil estabelecimentos agropecuários do estado.
- A agricultura familiar era responsável por quase a metade (48%) do valor total da produção agropecuária paraibana, alcançando um resultado de R$ 1,076 bilhão. Essa participação variava de 23%, no Território da Mata Sul e no Território da Mata Norte, a 76%, no Território do Alto Sertão.

- No Território da Serra do Teixeira, localizado na região nordeste do estado, os estabelecimentos da agricultura familiar respondiam por 85% do total de estabelecimentos agropecuários. A menor presença relativa de estabelecimentos da agricultura familiar (72%) se dá no Território da Borborema, embora, em termos absolutos, seja o território com maior número de estabelecimentos familiares (mais de 30 mil). Na Borborema também está o maior número de agricultores não familiares (11.524).
- O elevado número de estabelecimentos indica a importância da agricultura familiar para a dinâmica econômica da produção rural paraibana e para subsistência das famílias envolvidas nesse modelo de produção, considerando-se a renda oriunda da atividade econômica do empreendimento familiar, assim como a produção para autoconsumo.
- Os estabelecimentos da agricultura familiar na Paraíba se concentravam nas áreas até 10 hectares (70,8% deles), sendo que 12,6% tinham área inferior a 1 ha e 16,3% tinham entre 1 e 2 hectares. Em áreas de até 20 hectares, estavam 84% de todos os estabelecimentos da agricultura familiar.
- Observa-se que 71,7% dos 125.489 estabelecimentos da agricultura familiar da Paraíba se dedicavam à produção de origem animal e 83,6% deles à produção de origem vegetal.
- Quanto aos territórios, 92,5% dos estabelecimentos da agricultura familiar no território do Médio Piranhas estavam dedicados à produção animal e, no Vale do Maringá, 91,5%. No município de Riacho de Santo Antônio, 100% dos estabelecimentos estavam dedicados à produção animal e, em Alcantil, 99,7%, ambos na Borborema.
- Os territórios com maior porcentagem de estabelecimentos familiares dedicados à produção vegetal eram a Mata Sul (94,1%); o Vale do Paraíba, com 93,7%, Piemonte da Borborema, com 92,9% e Serra do Teixeira, com 92,8%.
- A renda total obtida pelos estabelecimentos da agricultura familiar paraibana totalizou R$ 2,27 bilhões, sendo que o Território da Borborema teve a maior contribuição, com R$ 606,6 milhões (26,7% do total).
- Essa renda obtida pelos estabelecimentos da agricultura familiar na Paraíba se dividia em três tipos: a) receitas do estabelecimento com produção agropecuária; b) outras receitas do estabelecimento (desinvestimento, serviço de turismo rural, exploração mineral, atividade de artesanato, tecelagem etc. e demais receitas do estabelecimento); e c) outras receitas do produtor (aposentadorias e pensões; renda de atividades desenvolvidas fora do estabelecimento; renda proveniente de programas dos governos).
- Em 2017, a principal fonte de receita dos estabelecimentos da agricultura familiar foram os" Recursos de aposentadorias ou pensões", que alcançaram a cifra de R$ 1,155 bilhão, o equivalente a 51% do total de R$ 2,272 bilhões de todas as receitas. Esse resultado dá a dimensão da importância dessa fonte de renda para os/as agropecuaristas familiares.
- A segunda maior fonte foram as "Receitas da produção dos estabelecimentos", na ordem de R$ 861,6 milhões (37,9% do total das receitas), com destaque para a produção de "Animais e seus produtos", com uma receita de R$ 518 milhões.

- O Território da Borborema – que tem o maior número de municípios, 38 - foi o que apresentou os maiores valores da produção agricultura familiar (R$ 288,5 milhões, ou 27% do valor total da agricultura familiar no estado), seguido de longe pelo Território da Mata Sul, com 95,6 milhões (8,9% do valor total).
- Se, para o estado como um todo, o valor total da produção agricultura familiar foi de R$ 1,076 bilhão, o valor da produção familiar de origem animal foi de R$ 649,7 milhões (60,5% do total) e o valor da produção de origem vegetal foi de R$ 423,9 milhões (39,5% do total).
- Na produção de origem animal, os estabelecimentos da agricultura familiar na Paraíba se concentravam, principalmente, na criação de aves, com 54,1% dos estabelecimentos dedicados a essa atividade.
- A proporção de estabelecimentos dedicados à criação de animais de pequeno porte[13] era pequena, ocorrendo em apenas 0,5% dos estabelecimentos da agricultura familiar paraibana.
- A criação de animais de médio porte[14] estava presente em 23,4% dos estabelecimentos da agropecuária familiar, com destaque para os territórios do Cariri, com 46,9%, e Curimataú, com 34,6%.
- Na criação de animais de grande porte[15], estavam envolvidos 38,6% dos estabelecimentos da agricultura familiar da Paraíba.
- O maior valor da produção animal foi verificado na produção de animais de grande porte (R$ 436,9 milhões), com destaque para o Território da Borborema, com R$ 104,4 milhões (23,9% do valor total); seguido de longe pelo Vale do Piancó, com R$ 45,7 milhões (10,5%).
- Em 2017, 98.870 estabelecimentos (78,8% do total de 125.489 estabelecimentos da agricultura familiar do estado) se dedicavam à produção vegetal de lavouras temporárias. Nesses 98.870 estabelecimentos, a maior presença foi registrada no Território da Borborema - o maior da Paraíba, com 38 municípios -, onde 22.845 estabelecimentos (23,1% do total), cultivavam esse tipo de lavoura. Na sequência, aparecia, em um distante segundo lugar, o Território do Piemonte da Borborema, com 9.573 estabelecimentos (9,7% do total).
- As lavouras permanentes estavam presentes em 11.840 estabelecimentos (9,4% dos 125.489 estabelecimentos da agricultura familiar do estado). Entre esses 11.840 estabelecimentos, o destaque também ficou com o Território da Borborema, onde 3.496 estabelecimentos (29,5% do total), produziam lavouras permanentes.
- O valor da produção vegetal nos estabelecimentos da agricultura familiar da Paraíba é maior nas lavouras temporárias, onde alcançou a cifra de R$ 244,8 milhões, 3,7 vezes o valor da produção das lavouras permanentes.
- A Horticultura estava presente em 11.020 estabelecimentos (8,8% dos 125.489 estabelecimentos da agricultura familiar no estado). Entre esses 11.020 estabelecimentos com produção de hortaliças, le-

13. Coelhos, da apicultura, da sericicultura e da aquicultura.
14. Suínos, caprinos e ovinos.
15. Bovinos, bubalinos, equinos, asininos e muares.

gumes e frutas, destacou-se o Território da Mata Sul, com 3.110 estabelecimentos (28,2% do total), e o Território da Borborema, com 2.179 (19,8%).

- A Floricultura estava presente em apenas 51 estabelecimentos da agricultura familiar na Paraíba (0,04% dos 125.489 estabelecimentos da agricultura familiar do estado), com destaque novamente para o Território da Borborema, onde 22 estabelecimentos (43,1% dos estabelecimentos floricultores) produzem flores, e a Mata Sul, com 11 estabelecimentos (21,6%).
- A Silvicultura aparecia em 1.021 estabelecimentos, 0,8% do total de estabelecimentos da agricultura familiar do estado, com destaque para o Território da Borborema, com 368 estabelecimentos (36,0% do total) cultivando florestas através do manejo agrícola.
- Na extração vegetal, 18.659 estabelecimentos, 14,9% do total de estabelecimentos da agricultura familiar do estado, se dedicavam ao cultivo de produtos provenientes de espécies vegetais não plantadas (nativas). O Território da Borborema se destacava, com 5.742 estabelecimentos (30,8% do total de estabelecimentos extrativistas). No valor da extração vegetal, o destaque fica com a Borborema, com R$ 14,6 milhões (43,8% do total).
- Quanto à agroindústria familiar na Paraíba, entre os produtos mais comercializados, em 2017, destacaram-se o "queijo e requeijão", que representaram 61,5% (R$ 47,5 milhões) do valor total das vendas, de R$ 77,4 milhões.
- Em seguida apareceu o produto "carne de outros animais (verde)", com um valor de vendas de R$ 7,5 milhões (9,7% do total comercializado); seguido, pela "carne de bovinos (verde)", com R$ 6,6 milhões (8,5% das vendas); a "carne de suínos (verde), com vendas de R$ 4,3 milhões (5,6%); a "farinha de mandioca", com vendas de R$ 3,6 milhões (4,7% do total); e "doces e geleias", com vendas de R$ 2,4 milhões (3,1% do total das vendas). Esses seis produtos responderam por 93,1% de todas as vendas de produtos da agroindústria familiar no estado da Paraíba, em 2017, somando um valor de R$ 72 milhões.
- Os principais gastos dos estabelecimentos da agricultura familiar foram com a "Compra de animais", R$ 129,2 milhões (28,9% das despesas totais); "Salários pagos", R$ 91,3 milhões (20,4%); "Combustíveis e lubrificantes", R$ 91,1 milhões (20,3%); "Energia elétrica", R$ 78,2 milhões (17,5%); "Adubos e corretivos", R$ 50,5 milhões (11,3%); e "Agrotóxicos", R$ 7,4 milhões (1,7%). A despesa total somou R$ 447,7 milhões.
- O peso dos gastos com "Compra de animais" reflete o fato de que o maior valor da produção da agricultura familiar na Paraíba provém da produção animal (60,5% do valor total).
- É interessante observar que a segunda maior despesa dos **estabelecimentos da agricultura familiar** da Paraíba, em 2017, era com **"Salários pagos",** praticamente no mesmo valor das despesas com "Combustíveis e lubrificantes". Outra despesa significativa nos estabelecimentos da agricultura familiar era com a "Energia elétrica". Juntas, essas quatro grandes despesas respondiam por 87,1% das despesas totais. Por fim, apareciam as despesas com "Adubos e corretivos" (11,3% da despesa total) e com a compra de agrotóxicos, esta última com participação de apenas 1,7% no total das despesas.

- A despesa com "Agrotóxicos" (R$ 7,4 milhões) adquiria importância mais destacada na Mata Sul, com R$ 1,5 milhão (20,1% da despesa total com esse item), talvez pela alta concentração da produção da horticultura nesse território. Na sequência, figuravam o Território da Mata Norte, com R$ 974 milhões gastos com "Agrotóxicos" (13,2%); e o Vale do Paraíba, com R$ 918 milhões (12,4%). Somente esses três Territórios responderam por quase a metade (45,7%) do valor gasto com agrotóxicos pelos estabelecimentos da agricultura familiar paraibana, em 2017.
- A utilização de agrotóxicos era relativamente semelhante, quando se compara a porcentagem de estabelecimentos da agricultura familiar (33,2%) e a porcentagem (28,2%) de estabelecimentos não familiares que usavam esses produtos, embora os dados não tratem da quantidade utilizada em cada grupo. Pelo valor dos gastos, conclui-se que muitos estabelecimentos da agricultura familiar utilizavam agrotóxicos, porém em quantidades pequenas, já que a despesa com esses produtos era módica.
- Entre os estabelecimentos da agropecuária familiar, a média da utilização de agrotóxicos foi de 33,2%, sendo que 66,6% dos estabelecimentos não os utilizaram. A maior utilização se deu no Vale do Piranhas, em 61,1% dos estabelecimentos, e no Médio Piranhas, em 60,7%. A menor utilização ocorreu no Cariri, em 9,4%.
- Entre os estabelecimentos da agropecuária não familiar, 28,2% usaram agrotóxicos e 71,6% não utilizaram. As maiores taxas de utilização se deram, também, no Vale do Piranhas, com 57,6%, e Médio Piranhas, com 55,7%. A menor taxa de utilização ocorreu no Cariri, com 7,6%.
- Declararam receber algum tipo de orientação técnica somente 16,8% dos 125.489 estabelecimentos da agricultura familiar da Paraíba, em 2017. Os territórios com maior porcentagem de estabelecimentos que receberam orientação técnica foram o Alto Sertão (44,3%); o Vale do Maringá (39,3%); e o Vale do Piranhas (35,1% dos estabelecimentos).
- Mais de 83% dos estabelecimentos da agricultura familiar paraibana não receberam qualquer orientação técnica, em 2017. Esse percentual superava os 80% em 11 dos 15 Territórios. A maior porcentagem desses estabelecimentos estava no Território da Mata Sul (91,7%).
- Em relação à oferta de orientação técnica, destacava-se o papel relevante dos governos (federal, estadual ou municipais). Na Paraíba, 13,5% dos estabelecimentos da agricultura familiar receberam alguma orientação técnica por parte desses órgãos, com destaque para o Vale do Maringá, onde somavam 38,1%.
- Outras fontes de orientação técnica tiveram importância mais modesta. A orientação do próprio produtor foi informada por 2,3% dos estabelecimentos da agropecuária familiar, com destaque para o Território do Alto Sertão, com 13,5% dos estabelecimentos; a orientação por parte das cooperativas foi informada somente por 0,8% deles; e das Empresas/ONGs ou Sistema "S" por apenas 0,5%.
- Quanto aos atributos pessoais dos responsáveis pelos estabelecimentos da agricultura familiar na Paraíba, observa-se, em primeiro lugar, que a atividade econômica era exercida predominantemente

por trabalhadores do sexo masculino (76% do total). As maiores porcentagens de participação das mulheres como responsáveis pelos estabelecimentos da agricultura familiar se davam nos territórios da Mata Norte (32,3%) e Borborema (31,2%). As menores nos Território do Vale do Piancó (12,4%) e Médio Piranhas (14,0%).

O Censo Agropecuário de 2017, pela primeira vez, investigou a cor da pele dos/as produtores/as responsáveis pelos estabelecimentos da agricultura familiar. Sob esse aspecto, mais da metade dos/as responsáveis se declarou de cor parda (56% do total), com destaque para os Territórios do Piemonte da Borborema e Serra do Teixeira, onde 64,1% e 62,0%, respectivamente, se declararam desta cor.

O percentual de estabelecimentos cujos responsáveis se declararam da cor branca foi de 34,6%, com destaque para o Território do Médio Piranhas, onde os brancos representavam 47,2% dos responsáveis. Em terceiro lugar, em 7,7% dos estabelecimentos, os responsáveis se declararam pretos, com destaque para o Território da Mata Sul (13,5%). O contingente que se declarou indígena não chegou a 1%, com destaque para o Território da Mata Norte, com 14,3%. Os que se declararam amarelos eram 0,4%, com destaque para o Médio Sertão, com 2,2% dos responsáveis pelos estabelecimentos da agropecuária familiar.

Quanto à faixa etária dos responsáveis pelos estabelecimentos da agricultura familiar paraibana, observa-se que 22,7% dos estabelecimentos (cerca de 28 mil) eram dirigidos por responsáveis com idade entre 55 e 65 anos. Outros 30,3% (cerca de 38 mil) eram dirigidos por produtores com idade acima de 65 anos. Ou seja, mais da metade (53%) dos estabelecimentos da agricultura familiar na Paraíba eram dirigidos por produtores com 55 anos ou mais, já na idade da aposentadoria como segurado especial pelo Instituto Nacional do Seguro Social (INSS). Esses números evidenciam um problema da agricultura familiar na Paraíba - na verdade em todo o Brasil -, que é o envelhecimento dos produtores familiares rurais, a baixa renovação por produtores mais novos e as dificuldades na sucessão da propriedade, tornando o envelhecimento um agravante social entre esses produtores.

O nível de escolaridade dos responsáveis pelos estabelecimentos da agricultura familiar da Paraíba demonstra que quase ¼ (24,2%) deles nunca frequentou a escola, com destaque para os Territórios do Vale do Piancó (35,8%) e da Mata Norte, com 34,3%. No município de Olho D´Água, no Vale do Piancó, 63,4% dos responsáveis não eram alfabetizados. Em São Domingos, no Vale do Maringá, 57,4% dos responsáveis pelos estabelecimentos da agricultura familiar nunca frequentaram a escola.

Outros 47,5% dos responsáveis pelos estabelecimentos da agricultura familiar na Paraíba tinham cursado apenas até a quinta série do Ensino Fundamental ou equivalente, com destaque para o Alto Sertão, com 57,7%. Em seguida, 19,4% dos responsáveis tinham o Ensino Fundamental completo ou equivalente; 7,5% tinham o Ensino Médio ou equivalente; e apenas 1,3% tinham o Ensino Superior, Mestrado ou Doutorado.

A condição do responsável pelo estabelecimento agropecuário familiar em relação à posse da terra[16] era, principalmente, a de proprietário, em 72,6% do total dos 125.489 estabelecimentos. Destaque para os territórios da Serra do Teixeira, com 84,7%, e do Cariri, com 83,3%.

Com acesso mais precário a terras estavam os outros 34.360 responsáveis pelos estabelecimentos da agricultura familiar, ou 27,4% do total. Os Concessionários(as) ou os Assentados(as) aguardando titulação definitiva[17] (7,6% do total) destacavam-se no Território da Mata Sul, com 25,2%, e Vale do Paraíba, com 13,7%. Na Mata Sul, o município de Sapé tinha 51,1% dos 1.328 responsáveis pelos estabelecimentos da agricultura familiar nessa condição; Caaporã tinha 48,3% dos responsáveis pelos seus 396 estabelecimentos e Cruz do Espirito Santo tinha 39,2% dos 1.325 responsáveis pelos estabelecimentos. Na Mata Norte, também se destacavam os municípios de Marizópolis, com 69% dos 158 responsáveis pelos estabelecimentos, e Baía da Traição, com 59% dos 441 responsáveis. E o município de São Miguel do Taipu, no Vale do Paraíba, com 57,3% dos 606 responsáveis pelos estabelecimentos. No total, eram 29 municípios com mais de 20% dos responsáveis pelos seus estabelecimentos nessa condição.

A presença de arrendatários[18] entre os responsáveis pelos estabelecimentos da agricultura familiar era pequena (1,6%), com exceção do município de Bayeux, onde 66,7% dos responsáveis pelos 18 estabelecimentos estavam nessa condição. Entre os parceiros[19], a presença de estabelecimentos da agricultura familiar também é pequena (3,1% dos responsáveis), sendo que somente no Território do Médio Piranhas o percentual é mais elevado, chegando a 12,1%.

Os Comodatários[20] eram responsáveis por 12% dos estabelecimentos da agricultura familiar paraibana. As maiores participações verificavam-se nos Territórios do Vale do Paraíba, com 18,3%, e Vale do Piranhas, com 16,1%. No Município de Santa Rita, 48,1% de seus 320 estabelecimentos eram de comodatários. Nos municípios de Gabo Bravo, Borborema, e Salgadinho, os comodatários estavam presentes em 44,4% dos estabelecimentos da agricultura familiar.

Quanto à ocupação, os estabelecimentos agropecuários da Paraíba ocupavam 424.056 pessoas, sendo 311.176 (73,4%) em estabelecimentos familiares e 112.880 (26,6%) em estabelecimentos não familiares.

A Borborema era o território com maior número de ocupados: 107 mil, no total, sendo 76.640 nos estabelecimentos da agropecuária familiar. Ainda em relação aos estabelecimentos da agropecuária familiar, a Borborema também aparece com o maior número de trabalhadores temporários (5.927) e permanentes (980).

16. A condição do proprietário foi acatada independentemente da dimensão ou da proporção das terras do estabelecimento que se enquadrasse na situação terras próprias. Não havendo terras próprias, a condição do produtor seria aquela que, obedecida a ordem das categorias, correspondesse à maior porcentagem da área das terras do estabelecimento.
https://biblioteca.ibge.gov.br/visualizacao/periodicos/3096/agro_2017_resultados_definitivos.pdf
17. Produtor com área de terras concedidas por órgão fundiário, sem título definitivo (inclusive assentamento e com concessão de direito real de uso) até a data de referência.
18. Produtor que explora terras de terceiros, mediante pagamento de uma quantia fixa, previamente ajustada, em dinheiro ou sua equivalência em produtos.
19. Produtor que explora terras de terceiros, mediante pagamento de parte da produção (meia, terça, quarta etc.), previamente acordado entre as partes.
20. Produtor que explora terras de terceiros gratuitamente mediante contrato ou acerto entre as partes, no qual somente o comodatário assume as obrigações.

Nos estabelecimentos da agropecuária familiar, o pessoal ocupado compunha-se, principalmente, de trabalhadores/as com laços de parentesco com o produtor responsável pelo estabelecimento[21] (274.971 pessoas), 88,4% do total ocupado nesses estabelecimentos. Entre os que não possuíam laços de parentesco com os produtores familiares responsáveis, os trabalhadores temporários aparecem em maior número, com 32.440 ocupados, 10,4% do total na agropecuária familiar. Os trabalhadores permanentes eram apenas 3.235 (1%) dos ocupados e os parceiros somavam 530 trabalhadores (0,2%).

21. Cônjuge ou companheiro(a) do mesmo sexo ou de sexo diferente, filho(a) do produtor e do cônjuge, filho(a) somente do produtor, filho(a) somente do cônjuge, genro ou nora, pai, mãe, padrasto, madrasta, sogro(a), neto(a), bisneto(a), irmão ou irmã, avô(ó), outros parentes (tio/a, sobrinho/a, primo/a, cunhado/a, ou menor sob guarda ou tutela), e enteado(a) do produtor. Foram considerados, também, neste contexto, os agregados que, apesar de não terem laços de parentesco com o núcleo familiar, são considerados por seus membros como integrantes da família.

ANEXO

Mapa 1: *Mapa dos estabelecimentos agropecuários*
Paraíba, 2017

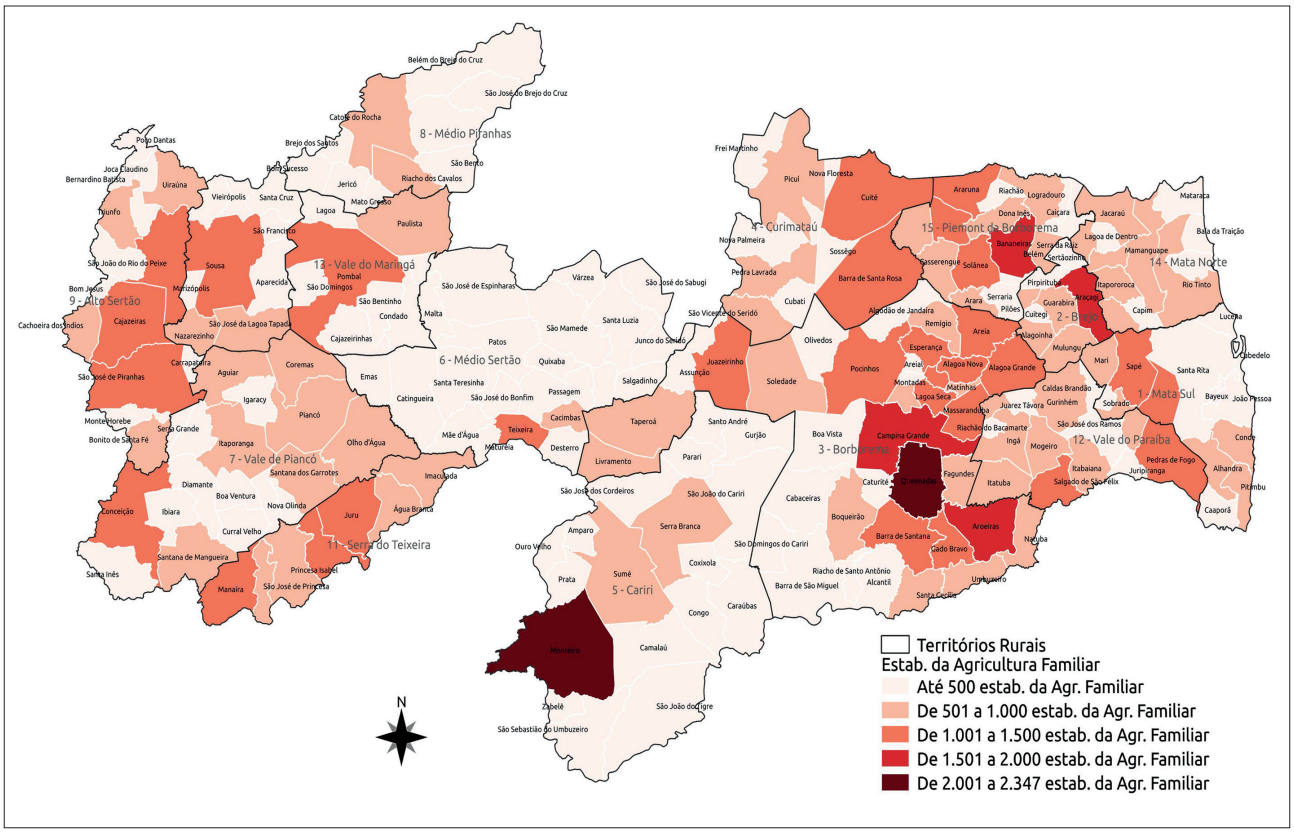

Fonte: Censo Agropecuário/IBGE, 2017
Elaboração: DIEESE
Nota: Tabela 6755 do SIDRA-IBGE.
https://sidra.ibge.gov.br/pesquisa/censo-agropecuario/censo-agropecuario-2017

Mapa 2: *Mapa dos estabelecimentos agropecuários*
Paraíba, 2017

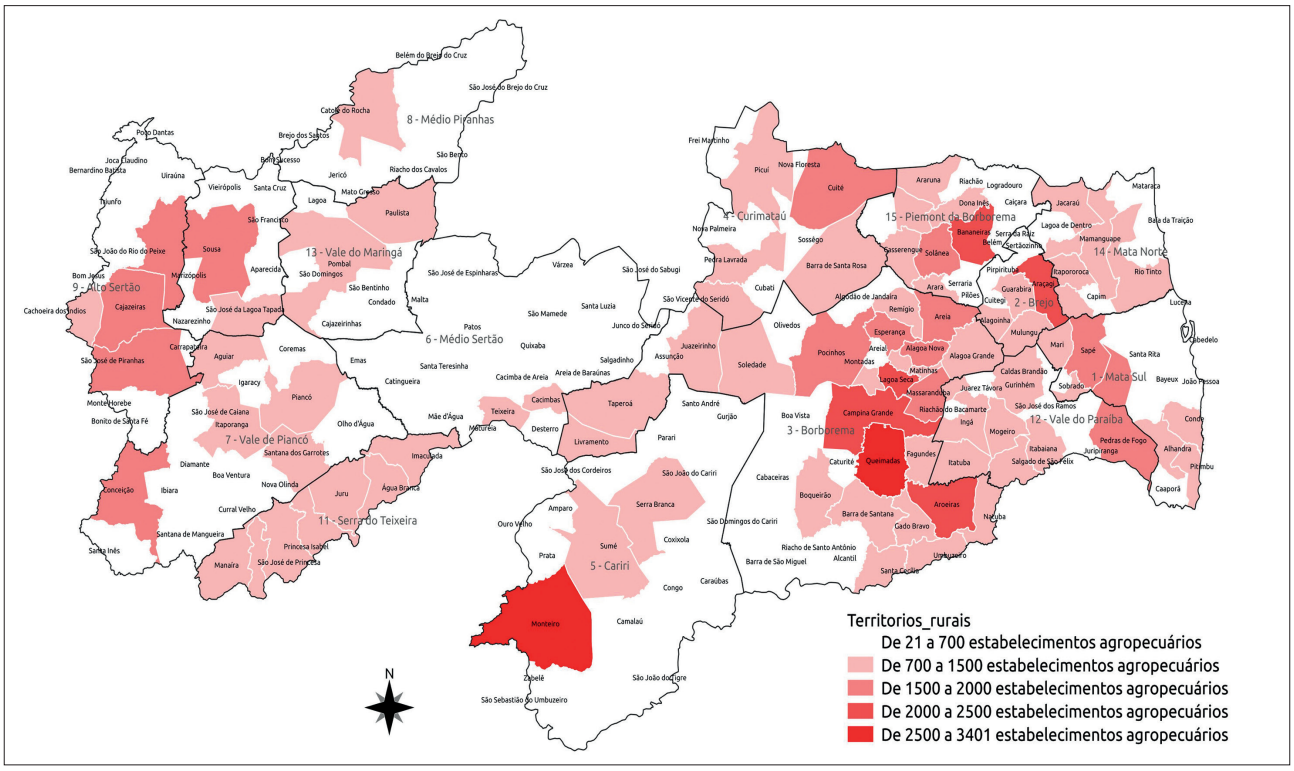

Fonte: Censo Agropecuário/IBGE, 2017
Elaboração: DIEESE
Nota: Tabela 6755 do SIDRA-IBGE.
https://sidra.ibge.gov.br/pesquisa/censo-agropecuario/censo-agropecuario-2017